Licensed to: Nicolò Guffanti (vss@tramos.ch) / Downloaded 03.04.2026

REGnorm
Nationales Register zur Veröffentlichung von Normen, Standards und weiteren Regulierungen
Registre national pour la publication de normes, standards et autres réglementations
Registro nazionale per la pubblicazione di norme, standard e altre regolamentazioni
National register for the publications of standards and other regulations

VSS 40 273

Norm
Norme
Norma
Standard

Remplace:
VSS 40 273a:2019-03

Edition: 2024-09

Carrefours

Conditions de visibilité dans les carrefours à niveau (hors giratoires)

La présente norme est de la compétence de la Commission de normalisation et de recherche (CNR) 2.2 Carrefours de la VSS.

N° de réf.:
VSS 40 273:2024-09 fr

Valide dès le:
2024-09-30

Droit d'auteur:
REGnorm, Nationales Register zur Veröffentlichung von Normen, Standards und weiteren Regulierungen

Coordinateur de la publication:
Schweizerischer Verband der Strassen- und Verkehrsfachleute VSS

Nombre de pages:
14

© REGnorm

Licensed to: Nicolò Guffanti (vss@tramos.ch) / Downloaded 03.04.2026

Elaboration

Commission de normalisation et de recherche VSS
CNR 2.2 Carrefours

Ont collaboré à l'élaboration de la norme

Broye Alain, Fribourg, autorités et pouvoirs publics
Cuttelod David, Lausanne, utilisateur des normes
Freudenthaler Cindy, Pully, autorités et pouvoirs publics
Giovannacci Emanuele, Berne, organisations non gouvernementales/ONG
Meyer Florian, Lausanne, utilisateur des normes
Passardi Gianola Lorenza, Lugano, utilisatrice des normes
Genilloud Marc, Châtel-Saint-Denis, utilisateur des normes
De Gasparo Charles-Etienne, Berne, utilisateur des normes

Cette norme a été élaborée sur la base des connaissances actuelles dans les domaines de la sécurité et du développement durable.

Approbation

Commission technique VSS
CT 2 Etude de projets

Publication

Septembre 2024

Exclusion de responsabilité

Aucune responsabilité n'est assumée pour les dommages qui pourraient résulter de l'utilisation de cette publication.

© REGnorm

Licensed to: Nicolò Guffanti (vss@tramos.ch) / Downloaded 03.04.2026

TABLE DES MATIÈRES Page

A	**Généralités**	4
1	*Domaine d'application*	4
2	*Objet*	4
3	*But*	4
B	**Définitions**	4
4	*Distance de visibilité aux carrefours*	4
5	*Distance d'observation*	4
6	*Lignes de visibilité*	4
7	*Champ de vision*	4
8	*Effet de palissade*	4
9	*Perceptibilité*	4
C	**Hypothèses et exigences**	6
10	*Bases et hypothèses*	6
11	*Exigences relatives au champ de vision*	7
D	**Conditions de visibilité nécessaires aux carrefours sans priorité de droite**	7
12	*Distances d'observation*	7
13	*Distances de visibilité*	8
	13.1 Véhicules automobiles	8
	13.2 Engins assimilés à des véhicules et piétons	8
	13.3 Trafic cycliste	9
14	*Mesures en cas de distance de visibilité insuffisante aux carrefours*	9
E	**Conditions de visibilité nécessaires aux carrefours avec priorité de droite**	10
15	*Condition préalable*	10
16	*Distances de visibilité et d'observation*	10
17	*Relation entre perceptibilité et distance de visibilité aux carrefours*	11
18	*Appréciation de la perceptibilité*	12
	18.1 Bons exemples	12
	18.2 Mauvais exemples	13
F	**Bibliographie**	14

© REGnorm

Licensed to: Nicolò Guffanti (vss@tramos.ch) / Downloaded 03.04.2026

A Généralités

1 *Domaine d'application*

Cette norme est applicable à toutes les routes avec carrefours à niveau, aux intersections et aux accès, y compris les accès riverains.
Pour les carrefours giratoires, la visibilité est traitée dans la VSS 40 263 «Carrefours; carrefours giratoires» [6].

2 *Objet*

La norme définit les dimensions du champ de vision dans les carrefours pour permettre aux véhicules non prioritaires de détecter et croiser le trafic prioritaire ou de s'y insérer.

3 *But*

La norme sert à évaluer les conditions de visibilité dans les carrefours à niveau. Le respect des distances de visibilité nécessaires aux carrefours est une garantie de sécurité pour l'ensemble des usagers de la route.

B Définitions

Les définitions suivantes sont illustrées aux figures 1 et 2. Elles s'appliquent aux conditions de visibilité dans les carrefours à niveau sans piste cyclable (figure 1) et avec piste cyclable (figure 2).

4 *Distance de visibilité aux carrefours*

La distance de visibilité A aux carrefours est la distance nécessaire pour que le véhicule non prioritaire F_B puisse s'engager sur l'axe prioritaire sans entrer en conflit avec le véhicule prioritaire F_A. Elle est mesurée sur l'axe de la voie de circulation du véhicule prioritaire F_A et correspond à la distance entre le véhicule prioritaire F_A et le point d'intersection entre l'axe prioritaire et celui qui ne l'est pas.

5 *Distance d'observation*

La distance d'observation B est la distance entre le point d'observation D et le bord le plus rapproché de la voie de circulation prioritaire ou le bord avant de la ligne d'arrêt ou d'attente.

6 *Lignes de visibilité*

Les lignes de visibilité S sont les droites reliant le point d'observation D aux véhicules F_A. La ligne de visibilité S' est applicable hors localité lorsque le dépassement est autorisé dans la zone du carrefour. S'' est la ligne de visibilité pour les infrastructures du trafic cycliste.

7 *Champ de vision*

Le champ de vision est la surface comprise entre les lignes de visibilité et les axes des voies de circulation prioritaires.

8 *Effet de palissade*

Le terme «effet de palissade» fait référence à l'effet provoqué par des éléments qui se suivent de près dans le champ de vision et qui ont pour effet de masquer les véhicules sur la chaussée prioritaire.

9 *Perceptibilité*

Dans cette norme, la perceptibilité d'un carrefour dans l'espace routier signifie sa qualité à être identifié visuellement par les usagers de la route.

© REGnorm

Licensed to: Nicolò Guffanti (vss@tramos.ch) / Downloaded 03.04.2026

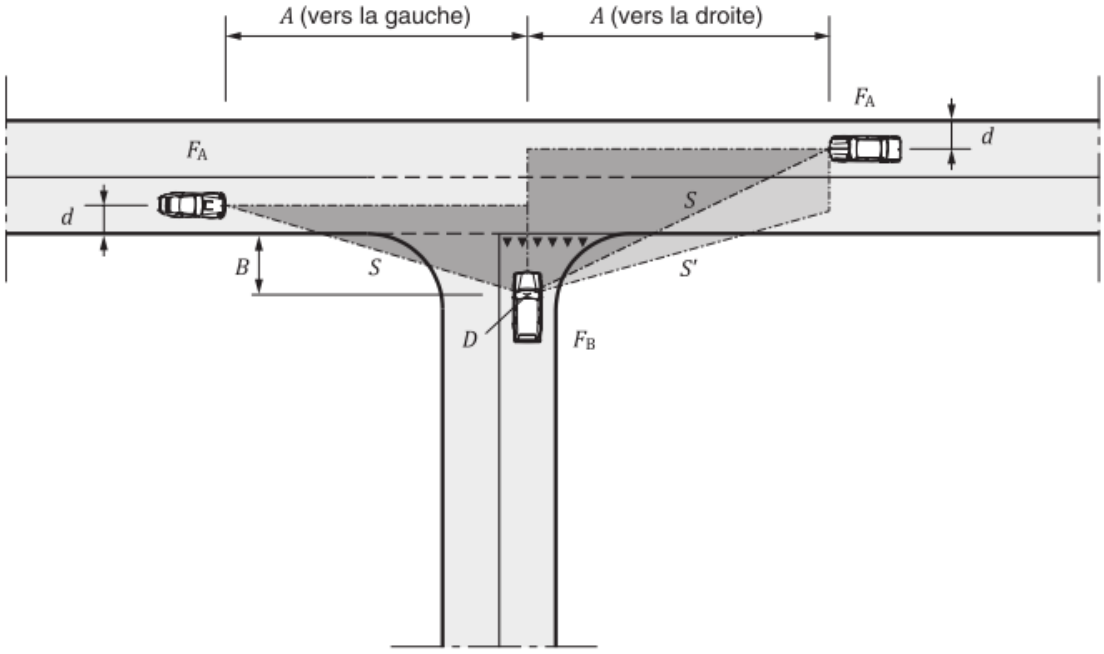

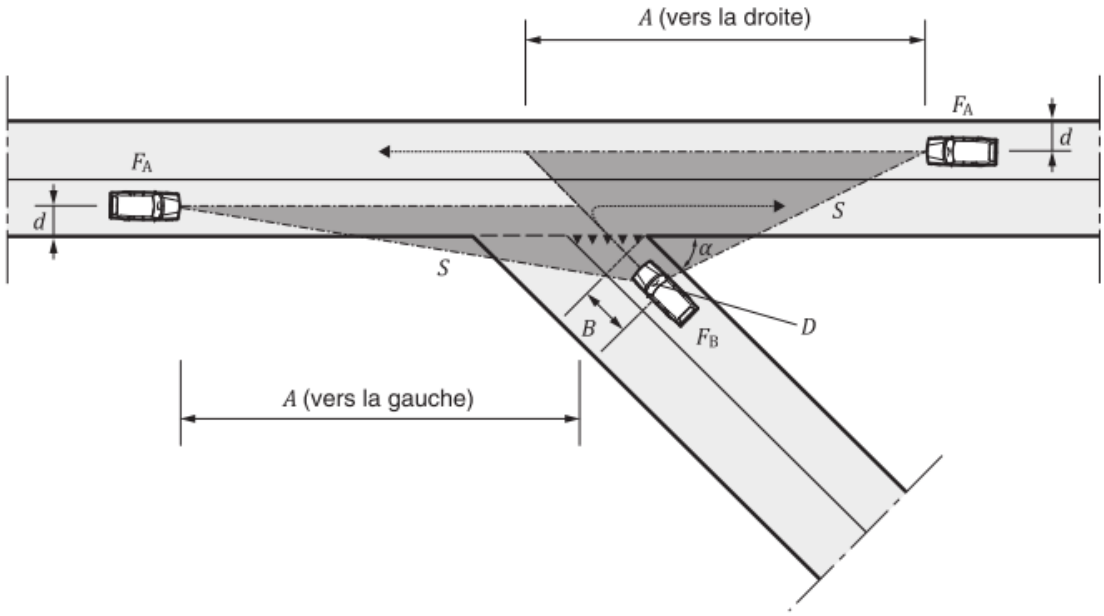

A	Distance de visibilité
B	Distance d'observation
S	Ligne de visibilité
S'	Ligne de visibilité en cas de dépassement
F_A	Véhicule prioritaire
F_B	Véhicule non prioritaire
D	Point d'observation
d	Distance entre l'axe médian du véhicule et le bord de la chaussée
α	Angle d'insertion
	Champ de vision par rapport à la chaussée
	Champ de vision en cas de dépassement dans la zone du carrefour

Fig. 1
Conditions de visibilité dans les carrefours sans piste cyclable

© REGnorm

Licensed to: Nicolò Guffanti (vss@tramos.ch) / Downloaded 03.04.2026

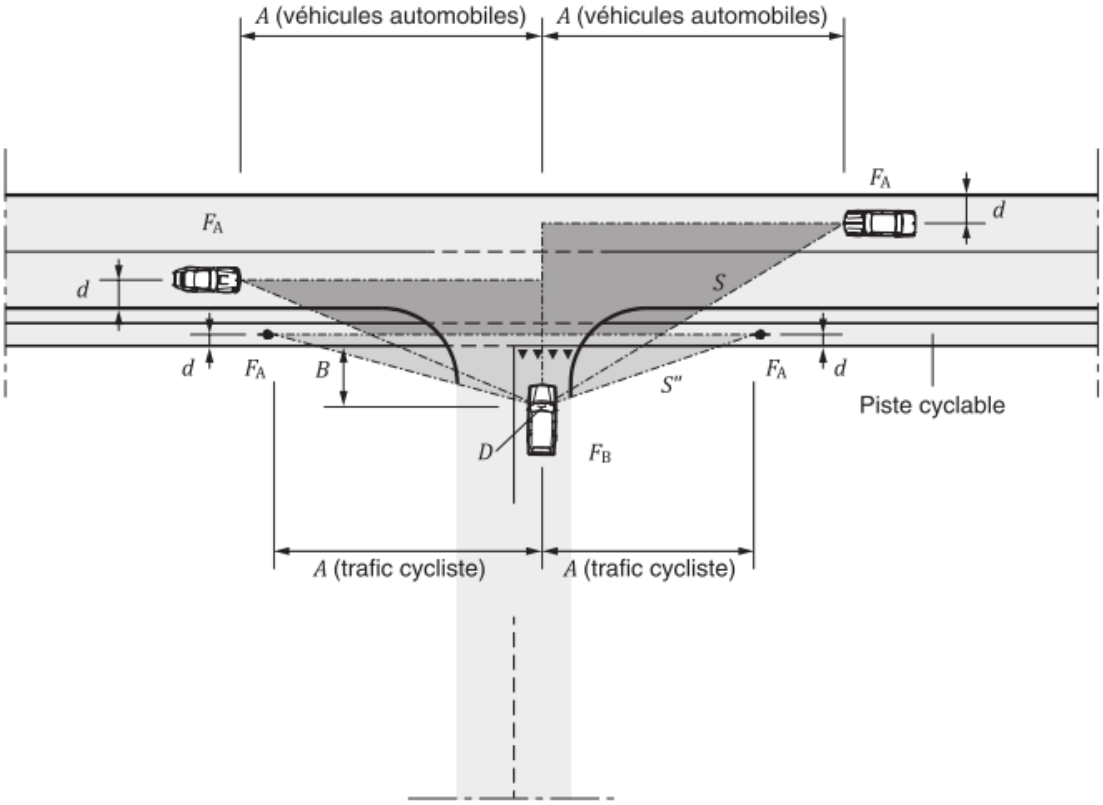

A	Distance de visibilité
B	Distance d'observation du trafic cycliste
S	Ligne de visibilité des véhicules automobiles
S''	Ligne de visibilité du trafic cycliste
F_A	Véhicule prioritaire
F_B	Véhicule non prioritaire
D	Point d'observation
d	Distance entre l'axe médian du véhicule ou du trafic cycliste et le bord de la chaussée
	Champ de vision par rapport à la chaussée
	Champ de vision par rapport à la piste cyclable

Fig. 2
Conditions de visibilité dans les carrefours avec piste cyclable

C Hypothèses et exigences

10 *Bases et hypothèses*

Comme bases et hypothèses, on observera les points suivants

- Les véhicules F_A circulent avec une vitesse donnée sur la route prioritaire en direction du carrefour; le véhicule F_B s'en approche en circulant sur la route sans priorité; les yeux du conducteur se trouvent au point D.
- La vitesse d'approche déterminante du véhicule prioritaire F_A s'approchant du carrefour est la plus petite des deux valeurs suivantes: vitesse maximale autorisée ou vitesse de projet V_P. Si la V_{85} est connue, les valeurs correspondantes peuvent être considérées.
- En cas de mesures constructives destinées à la modération du trafic, c'est la vitesse maximale effective praticable dans la zone du carrefour qui sera prise en compte (p.ex. en raison du passage sur des éléments constructifs de modération) selon la VSS 40 213 «Conception de l'espace routier; éléments de modération du trafic» [5].
- Les distances d'observation B (chiffre 12) et de visibilité A (chiffre 13) des carrefours découlent du rapport de recherche [14] pour les carrefours sans priorité de droite et de l'étude [12] pour les carrefours à priorité de droite.

© REGnorm

Licensed to: Nicolò Guffanti (vss@tramos.ch) / Downloaded 03.04.2026

– La distance d entre l'axe médian du véhicule automobile F_A et le bord droit de la chaussée est en général de 1,50 m (figure 1); pour le trafic cycliste sur routes à trafic mixte, elle est de d 0,50 m. Sur les infrastructures cyclables d est égal à la moitié de la largeur de la bande cyclable, de la piste cyclable ou du chemin pour piétons avec vélos admis (figure 2).
– La hauteur des yeux peut, selon l'usager de la route, se situer entre 1,00 m (voitures de tourisme) et 3,00 m (camions) au-dessus de la chaussée.
– Les angles d'insertion α nettement supérieurs ou inférieurs à 90° doivent en principe être évités. Une attention particulière doit être accordée aux angles d'insertion α compris entre 0° et 90°, car ils sont particulièrement problématiques pour les poids lourds (figure 1).

11 Exigences relatives au champ de vision

Les conditions permettant une visibilité conforme aux bases énoncées sous chiffre 10 doivent être garanties aussi bien dans le plan que dans l'espace. En principe, le champ de vision doit être libre de tout obstacle de nature à masquer les autres usagers de la route sur une hauteur comprise entre 0,60 m et 3,00 m mesurée au-dessus du niveau de la chaussée. Cette exigence s'étend notamment à la végétation, aux arbres, aux candélabres, à la neige, aux panneaux publicitaires, aux véhicules en stationnement, etc. et, dans la mesure du possible, aux signaux et panneaux de direction.
Dans des cas particuliers tels que les arbres d'alignement, les clôtures et les garde-corps, leurs éléments situés dans le champ de vision sont autorisés à condition que l'«effet de palissade» correspondant soit analysé. En particulier, il faut considérer qu'à la distance de visibilité A, le véhicule prioritaire doit être visible et que les zones, où le champ de vision est restreint, doivent être limitées et masquer le moins possible les véhicules ou le trafic cycliste (figure 3). Les caractéristiques et les géométries des arbres d'alignement doivent être évaluées conformément à la VSS 40 677 «Arbres d'alignement; bases» [7].

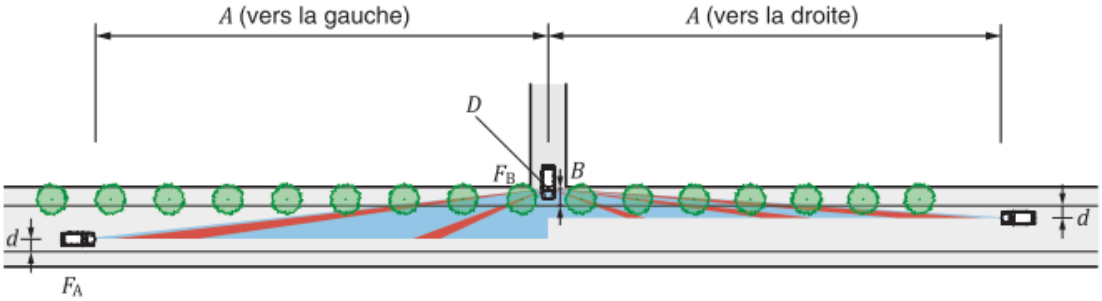

A Distance de visibilité
B Distance d'observation
D Point d'observation
d Distance entre l'axe médian du véhicule ou du trafic cycliste et le bord de la chaussée
F_A Véhicule prioritaire
F_B Véhicule non prioritaire
Champ de vision
Champ de vision restreint en présence d'arbres

Fig. 3
Exemple d'analyse de l'effet de palissade

D Conditions de visibilité nécessaires aux carrefours sans priorité de droite

12 Distances d'observation

Les distances d'observation B suivantes sont recommandées pour les véhicules automobiles et le trafic cycliste

– En localité, B est de 3,00 m
La distance d'observation ne doit pas être inférieure à la distance entre l'avant du véhicule et la position du conducteur du véhicule. La distance B de 3,00 m permet de tenir compte de la quasi totalité des types de véhicules immatriculés en Suisse selon [16].

– Hors localité, B est de 5,00 m ou 3,00 m
En raison des vitesses plus élevées, nécessitant un champ de vision plus important, la distance B est fixée à 3,00 m lorsque l'arrêt est nécessaire et à 5,00 m pour tous les autres cas.

© REGnorm

Licensed to: Nicolò Guffanti (vss@tramos.ch) / Downloaded 03.04.2026

La distance d'observation B ne doit pas être inférieure à 3,00 m. Des exceptions pour les carrefours et les accès existants sont indiquées sous chiffre 14.
Les pistes cyclables situées à moins de 2,00 m du bord de la chaussée sont en principe assujetties aux mêmes règles de priorité que la route qu'elles longent. La distance d'observation B se mesure alors à partir du bord de la piste cyclable (figure 2).

13 Distances de visibilité

Les tableaux 1, 2 et 3 récapitulent les distances de visibilité A nécessaires aux carrefours.

13.1 Véhicules automobiles

Les distances minimales de visibilité A aux carrefours, applicables aux véhicules automobiles, sont définies par les domaines de valeurs données au tableau 1

- Les valeurs inférieures correspondent à la distance de visibilité d'arrêt selon la VSS 40 090 «Projets, bases; distances de visibilité» [4]. Elles sont données pour des routes à très faible déclivité ($i \leq \pm 2\%$) et s'appliquent aux types de routes de faible importance selon la VSS 40 040 «Projet, bases; types de route» [1], à savoir: routes de desserte RD, routes collectrices RC, et routes de liaison RL selon les VSS 40 043 «Projet, bases; type de route: routes de liaison» [2] et VSS 40 045 «Projet, bases; types de route: routes de desserte» [3].
- Les valeurs intermédiaires sont nécessaires pour les types de routes de catégorie supérieure, tels que les routes principales RP et les routes de liaison RL importantes.
- Les valeurs supérieures s'appliquent aux routes importantes lorsque les conditions sont défavorables dans la zone du carrefour: forte déclivité, plus de deux voies de circulation, pourcentage élevé de véhicules lourds. Ces valeurs supérieures se fondent sur des observations aux carrefours selon le rapport de recherche [14].
- Si le véhicule doit traverser un trottoir pour s'engager sur la route prioritaire, il peut avancer jusqu'au bord de la chaussée si le trottoir est libre d'obstacle.

Distances minimales de visibilité aux carrefours nécessaires en fonction de la vitesse d'approche des véhicules automobiles prioritaires							
Vitesse d'approche [km/h]	20	30	40	50	60	70	80
Distance de visibilité A [m] nécessaire aux carrefours	10…20	20…35	35…50	50…70	70…90	90…110	110…140

Tab. 1
Distances minimales de visibilité aux carrefours nécessaires en fonction de la vitesse d'approche des véhicules automobiles prioritaires

13.2 Engins assimilés à des véhicules et piétons

Les conducteurs d'un véhicule qui traversent un trottoir (p.ex. dans le cas d'un trottoir traversant ou d'un accès riverain avec trottoir) doivent toujours avoir une vue d'ensemble des circulations sur celui-ci, notamment par rapport aux engins assimilés à des véhicules et piétons. Par analogie, la distance d'observation B est de 3,00 m en retrait par rapport à l'arrière du trottoir.

Les distances de visibilité A doivent respecter les valeurs minimales énumérées dans le tableau 2. Celles-ci tiennent compte du trafic piétonnier, des engins assimilés à des véhicules mais aussi des enfants jusqu'à 12 ans à vélo. Le reste du trafic cycliste autorisé selon l'art. 65, al. 8 OSR [11] n'est pas pris en compte.

Distances minimales de visibilité nécessaires aux trottoirs en fonction de la déclivité				
Déclivité [%]	≤ –6	–4	–2	≥ 0
Distance de visibilité A [m] nécessaire	30	20	20	15

Tab. 2
Distances minimales de visibilité nécessaires aux trottoirs en fonction de la déclivité [13]

© REGnorm

Licensed to: Nicolò Guffanti (vss@tramos.ch) / Downloaded 03.04.2026

13.3 Trafic cycliste

Le tableau 3 définit les valeurs nécessaires des distances de visibilité A aux carrefours, applicables au trafic cycliste sur des tronçons rectilignes [16]. Elles dépendent de la vitesse maximale autorisée et de la déclivité. Ces valeurs peuvent être réduites dans les tronçons en courbes, si les vitesses pratiquées sont réduites.

Distances minimales de visibilité A [m] nécessaires aux carrefours en fonction de la vitesse maximale autorisée et de la déclivité de la route prioritaire avec trafic cycliste				
Vitesse maximale autorisée [km/h]	Déclivité [%]			
	≤ –4	–2	0	> 0
≤ 30	30	25	25	20
> 30	55	55	50	45

Tab. 3
Distances minimales de visibilité A [m] nécessaires aux carrefours en fonction de la vitesse maximale autorisée et de la déclivité de la route prioritaire avec trafic cycliste [13], [15]

Dans les cas où les vélos électriques rapides sont interdits et où la vitesse maximale autorisée est > 30 km/h, on peut tenir compte d'une visibilité de 35 m en descente, de 30 m à plat et de 25 m en montée.

14 Mesures en cas de distance de visibilité insuffisante aux carrefours

En cas de distances de visibilité insuffisantes aux carrefours et accès existants, il convient en premier lieu de prendre des mesures proportionnées nécessaires pour atteindre les distances de visibilité figurant dans les tableaux 1 à 3 avec les distances d'observation selon le chiffre 12. Par mesure proportionnée, on entend p.ex. l'élagage ou l'enlèvement de la végétation, le remplacement de clôtures imperméables à la vue par des clôtures perméables, la suppression de places de stationnement ou l'arasement de talus. Si cela n'est pas possible avec un effort proportionné – p.ex. la suppression d'un mur de soutènement ou d'un angle de maison est nécessaire – on peut considérer les mesures suivantes (isolées ou combinées) qui, toutefois, ne sont pas admissibles pour des nouvelles constructions

- déplacer la ligne d'arrêt plus en avant, en prenant des mesures supplémentaires adéquates (p.ex. surface interdite, décalage de la ligne de bord)
- signaler un «Stop»
- introduire l'obligation de tourner à droite si la distance de visibilité depuis le point d'observation D n'est suffisante que vers la gauche
- sur les routes d'intérêt local selon la VSS 40 040 [1], modérer la vitesse en pavant la zone de carrefour ou en prenant d'autres dispositions appropriées conformément à la VSS 40 213 [5]
- abaisser la vitesse maximale autorisée sur la route prioritaire sous réserve d'une expertise selon l'OSR [11]
- installer des feux de circulation fonctionnant en permanence
- mettre en place un miroir seulement en dernier recours et aux conditions suivantes
  - la visibilité directe n'est atteinte qu'avec une distance d'observation inférieure à 1,50 m
  - uniquement avec un signal «Stop» ou à la sortie d'un accès riverain
  - avec une distance entre la ligne d'arrêt et le miroir inférieure à 15 m
  - avec un trafic faible sur la route non prioritaire
  - avec une limitation de vitesse autorisée sur la route prioritaire ≤ 60 km/h
  - avec une légalisation nécessaire pour l'emplacement du miroir
  - le bon fonctionnement d'un miroir doit être garanti même pendant les mois d'hiver
- supprimer l'accès dangereux

© REGnorm

Licensed to: Nicolò Guffanti (vss@tramos.ch) / Downloaded 03.04.2026

E Conditions de visibilité nécessaires aux carrefours avec priorité de droite

15 *Condition préalable*

L'application du régime de priorité de droite selon la Loi sur la circulation routière (LCR) [9] implique que les conducteurs de véhicules sont en mesure d'adapter leur vitesse à l'approche du carrefour, de manière à pouvoir s'arrêter si nécessaire avant le point de croisement selon l'Ordonnance sur les règles de la circulation routière (OCR) [10].
Le carrefour avec priorité de droite doit donc être facilement identifiable et perceptible en tant que tel.
Il devient par conséquent primordial d'améliorer au besoin la perceptibilité du carrefour afin d'assurer que l'usager de la route identifie rapidement le régime de priorité de droite et puisse adapter sa vitesse en conséquence (solutions proposées sous chiffres 16 et 17).
La vitesse mesurée à l'approche du carrefour est de 30 km/h ($V_{85\%}$ 28 km/h selon [12]).

L'application du régime de priorité de droite dans les carrefours est soumise aux conditions suivantes
- le standard d'aménagement et l'aspect général des branches doivent être semblables, comme c'est en général le cas pour les routes de desserte et les routes de liaison locales
- les charges de trafic des branches du carrefour doivent être du même ordre de grandeur

16 *Distances de visibilité et d'observation*

La sécurité à l'approche d'un carrefour avec priorité de droite découle de
- la perceptibilité du carrefour dans l'espace
- la distance de visibilité aux carrefours

Sans déclivité et avec une vitesse d'approche de 30 km/h selon [12], la distance de visibilité A nécessaire aux carrefours est supérieure à 20 m.
Dans le cadre d'un carrefour à priorité de droite avec une très bonne perceptibilité et si les conditions d'«état souhaité» ne peuvent être atteintes – voir chiffre 17 –, la distance minimale de visibilité A est fixée à 15 m, compte tenu des alignements et de la distance d'observation B (figure 4). Il en découle une distance d'observation B minimale de 5,00 m.

Si les prescriptions mentionnées ne peuvent pas être respectées et ne peuvent être réalisées qu'au prix d'efforts disproportionnés – voir chiffre 14 –, la priorité de droite doit être supprimée avec les mesures de signalisation correspondantes.

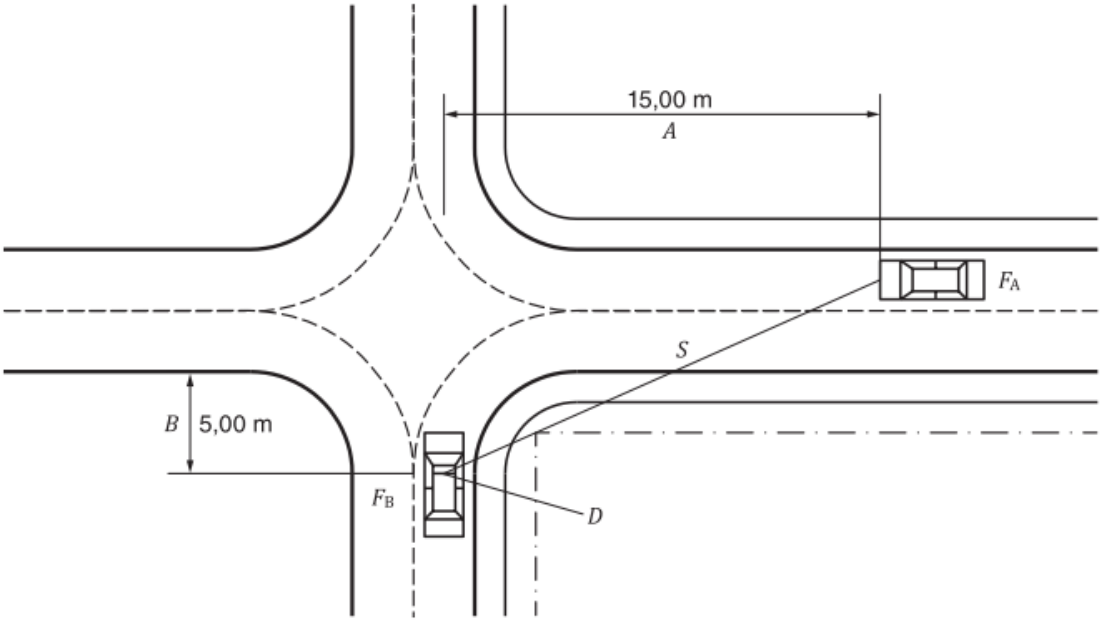

A Distance de visibilité
B Distance d'observation
S Ligne de visibilité
D Point d'observation
F_A Véhicule prioritaire
F_B Véhicule non prioritaire

Fig. 4
Distances de visibilité et d'observation dans les carrefours avec priorité de droite
(valeurs minimales pour un carrefour de très bonne perceptibilité)

© REGnorm

Licensed to: Nicolò Guffanti (vss@tramos.ch) / Downloaded 03.04.2026

Dans le cas de carrefours où les branches sont si étroites que deux voitures ne peuvent pas se croiser ($b \leq 3{,}50$ m), les conditions de visibilité décrites au préablable ne sont plus suffisantes pour assurer la sécurité. Dans ce cas, une distance d'arrêt de 20 m doit être garantie dans la zone du carrefour pour les deux véhicules, ce qui nécessite un champ de vision plus important encore (figure 5).

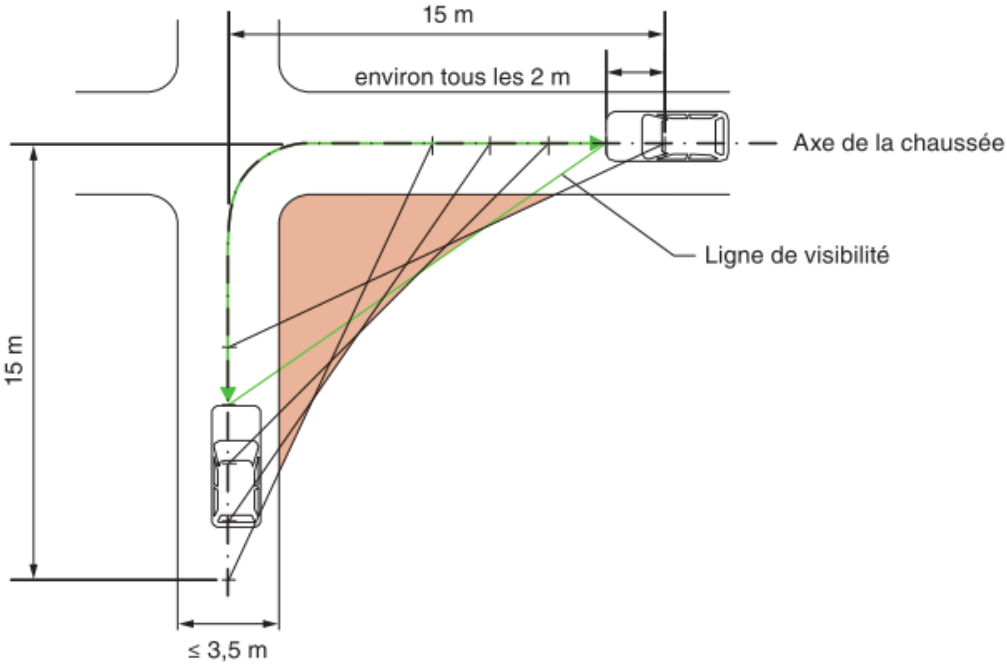

Champ de vision
Distance d'arrêt de 20 m, projetée environ tous les 2 m sur l'axe de la chaussée

Fig. 5
Distances de visibilité et d'observation dans les carrefours à branches étroites [12]

17 *Relation entre perceptibilité et distance de visibilité aux carrefours*

La sécurité des carrefours avec priorité de droite est étroitement liée à la relation entre
- la perceptibilité du carrefour et
- la distance de visibilité aux carrefours

De façon générale
- plus la perceptibilité est mauvaise, plus la distance de visibilité aux carrefours devra être grande
- inversement, plus la distance de visibilité aux carrefours est courte, meilleure devra être la perceptibilité

Cette relation est illustrée à la figure 6.

© REGnorm

Licensed to: Nicolò Guffanti (vss@tramos.ch) / Downloaded 03.04.2026

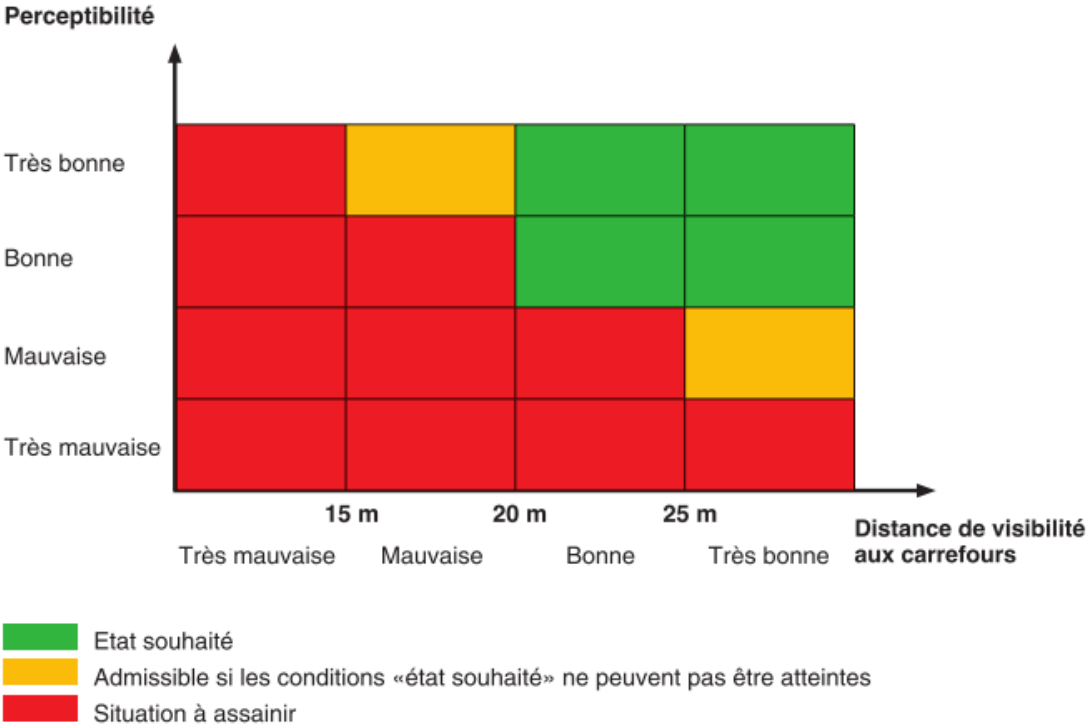

Fig. 6
Relation entre la perceptibilité et la distance de visibilité aux carrefours selon [12]

18 *Appréciation de la perceptibilité*

Un carrefour bien perceptible constitue l'élément clé en termes de sécurité routière des carrefours avec priorité de droite, car une bonne perceptibilité permet aux conducteurs de véhicules d'adapter leur vitesse de circulation. Cette notion est directement liée au tracé des routes dans la zone du carrefour, de l'aménagement des bords de la chaussée et de l'environnement construit aux alentours de celui-ci. Elle peut être classifiée de bonne ou mauvaise comme le présentent les figures 7 à 12.
En cas de mauvaise perception du carrefour, il est impératif de prendre des mesures afin d'améliorer sa perceptibilité.

18.1 Bons exemples

Les figures 7 à 9 présentent des exemples de bonne perceptibilité
- les haies ou les jardins sont discontinus de part et d'autre de l'intersection, ce qui indique clairement la présence du carrefour (cas A)
- le tracé du ou des trottoirs marque clairement la bifurcation (cas B, figure 8)
- des marques particulières selon la VSS 40 851 «Marques particulières; domaines d'application, formes et dimensions» [8] ou un aménagement routier de type décrochement vertical marque clairement le carrefour (cas C et D, figure 9)

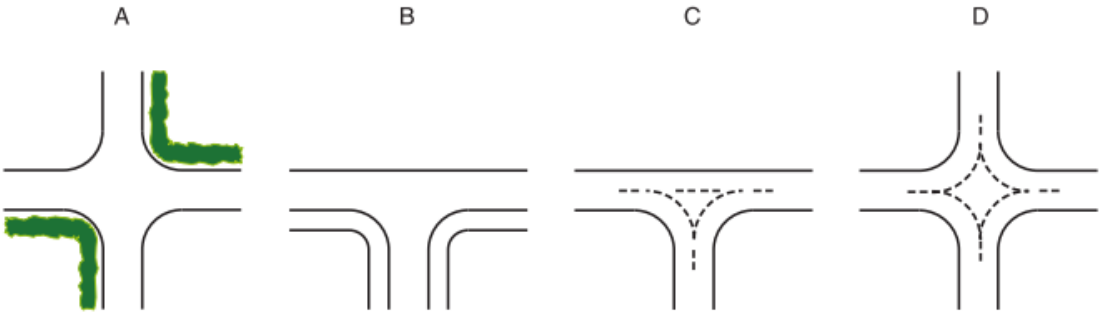

Fig. 7
Cas de figure de bonne perceptibilité

© REGnorm

Licensed to: Nicolò Guffanti (vss@tramos.ch) / Downloaded 03.04.2026

Fig. 8
Exemple de bonne perceptibilité: le tracé des trottoirs accentue la perceptibilité

Fig. 9
Exemple de bonne perceptibilité: accentuation du carrefour à l'aide de marques particulières

18.2 Mauvais exemples

Les figures 10 à 12 présentent des exemples de mauvaise perceptibilité
- les jardins qui bordent la chaussée se ressemblent et aucun trottoir ne marque la bifurcation (cas E et F, figure 11)
- un trottoir longe la route mais ne marque pas la bifurcation (cas G)
- un aménagement physique matérialisé par exemple par des pavés dans la zone de croisement donne une fausse impression de continuité (cas H, figure 12)

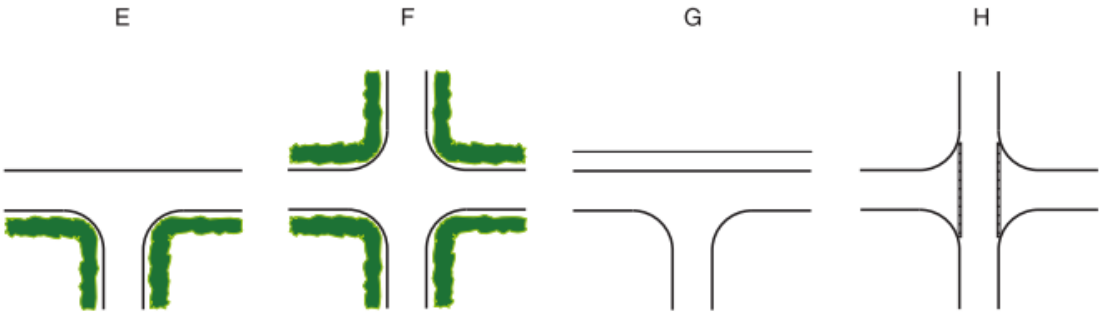

Fig. 10
Cas de figure de mauvaise perceptibilité

Fig. 11
Exemple de mauvaise perceptibilité: les bords de la chaussée se ressemblent

Fig. 12
Exemple de mauvaise perceptibilité: fausse impression de continuité donnée par la matérialisation d'un aménagement physique inapproprié

© REGnorm

Licensed to: Nicolò Guffanti (vss@tramos.ch) / Downloaded 03.04.2026

F Bibliographie

[1] VSS 40 040 Projet, bases; types de route
[2] VSS 40 043 Projet, bases; type de route: routes de liaison
[3] VSS 40 045 Projet, bases; types de route: routes de desserte
[4] VSS 40 090 Projets, bases; distances de visibilité
[5] VSS 40 213 Conception de l'espace routier; éléments de modération du trafic
[6] VSS 40 263 Carrefours; carrefours giratoires
[7] VSS 40 677 Arbres d'alignement; bases
[8] VSS 40 851 Marques particulières; domaines d'application, formes et dimensions
[9] RS 741.01 Loi fédérale sur la circulation routière (LCR), art. 36, al. 2
[10] RS 741.11 Ordonnance sur les règles de la circulation routière (OCR), art. 14, al. 1 et 2
[11] RS 741.21 Ordonnance sur la signalisation routière (OSR), art. 65, al. 8 et art. 108 al. 4 et 4bis
[12] Bureau suisse de prévention des accidents bpa; étude pilote, L'exploitation des croisements routiers régis par la priorité de droite, Berne, 1999
[13] Bureau suisse de prévention des accidents bpa; BM-021-2022 Visibilité aux carrefours et aux accès riverains, Berne, 2022
[14] Planungs- und Ingenieurbüro Hasler; Distances de visibilité et sécurité dans les nœuds, rapport de recherche nº 236. Meilen, 1992
[15] Office fédéral des route OFROU; Vélos électriques – effets sur le système de transports, rapport de recherche nº 1603. Berne, 2017
[16] www.autoschweiz.ch/Voitures_de_tourisme_ par_modele.html, Statistique selon modèles par trimestre ModellePWQuartal2009.xls

© REGnorm