Licensed to: Nicolò Guffanti (vss@tramos.ch) / Downloaded 26.03.2026

REGnorm
Nationales Register zur Veröffentlichung von Normen, Standards und weiteren Regulierungen
Registre national pour la publication de normes, standards et autres réglementations
Registro nazionale per la pubblicazione di norme, standard e altre regolamentazioni
National register for the publications of standards and other regulations

VSS 40 291

Norm
Norme
Norma
Standard

Ersetzt / Remplace:
VSS 40 291a:2019-03

Ausgabe / Edition: 2021-12

Parkieren

Anordnung und Geometrie der Parkierungsanlagen für Personenwagen und Motorräder

Stationnement

Disposition et géométrie des installations de stationnement pour voitures de tourisme et motocycles

Für diese Norm ist die Normierungs- und Forschungskommission (NFK) 2.1 Entwurf und Projektierung, Verkehrstechnische Bemessung, Fahrzeuggeometrie des VSS zuständig.

La présente norme est de la compétence de la Commission de normalisation et de recherche (CNR) 2.1 Conception et étude de projets, dimensionnement relatif à la circulation, géométrie des véhicules de la VSS.

Ref.-Nr. / N° de réf.:
VSS 40 291:2021-12 de/fr

Gültig ab / Valide dès le:
2021-12-31

Urheberrechte / Droit d'auteur:
REGnorm, Nationales Register zur Veröffentlichung von Normen, Standards und weiteren Regulierungen

Herausgeber / Coordinateur de la publication:
Schweizerischer Verband der Strassen- und Verkehrsfachleute VSS

Anzahl Seiten / Nombre de pages:
32

© REGnorm

Licensed to: Nicolò Guffanti (vss@tramos.ch) / Downloaded 26.03.2026

Bearbeitung

VSS-Normierungs- und Forschungskommission (NFK)
2.1 Entwurf und Projektierung, Verkehrstechnische Bemessung, Fahrzeuggeometrie

Liste der beteiligten Mitglieder

Dudler Felix, Biel, Normenanwender
Eberle Benedikt, Stettfurt, Behörden
Egger Bruno, Neukirch-Egnach, Normenanwender
Loosli Rolf, Freiburg, Behörden
Tille Micaël, Cottens FR, Normenanwender
Zumkehr Marco, Uttwil, Normenanwender

Diese Norm wurde gemäss dem aktuellen Wissensstand in den Bereichen der Sicherheit und der Nachhaltigkeit erarbeitet.

Genehmigung

VSS-Fachkommission (FK) 2
Projektierung

Publikation

Dezember 2021

Haftungsausschluss

Für Schäden, die durch die Anwendung der vorliegenden Publikation entstehen können, wird keine Haftung übernommen.

Elaboration

Commission de normalisation et de recherche VSS (CNR)
2.1 Conception et étude de projets, dimensionnement relatif à la circulation, géométrie des véhicules

Ont collaboré à l'élaboration de la norme

Dudler Felix, Bienne, utilisateur
Eberle Benedikt, Stettfurt, autorités et pouvoirs publics
Egger Bruno, Neukirch-Egnach, utilisateur
Loosli Rolf, Fribourg, autorités et pouvoirs publics
Tille Micaël, Cottens FR, utilisateur
Zumkehr Marco, Uttwil, utilisateur

Cette norme a été élaborée sur la base des connaissances actuelles dans les domaines de la sécurité et du développement durable.

Approbation

Commission technique VSS (CT) 2
Etude de projets

Publication

Décembre 2021

Exclusion de responsabilité

Aucune responsabilité n'est assumée pour les dommages qui pourraient résulter de l'utilisation de cette publication.

© REGnorm

Licensed to: Nicolò Guffanti (vss@tramos.ch) / Downloaded 26.03.2026

INHALTSVERZEICHNIS

		Seite
A	**Allgemeines**	5
1	*Geltungsbereich*	5
2	*Gegenstand*	5
3	*Zweck*	5
B	**Begriffe**	5
4	*Allgemeine Begriffe*	5
	4.1 Parkierungsanlage	5
	4.2 Parkhaus	5
	4.3 Einzelgarage	5
	4.4 Parkplatz	5
	4.5 Parkfeld	5
	4.6 Fahrgasse	6
	4.7 Fahrweg	6
	4.8 Rampe	6
	4.9 Einfahrt und Ausfahrt	6
	4.10 Parkfeldwinkel	6
	4.11 Überhangstreifen	6
	4.12 Schrammbord	6
C	**Voraussetzungen**	7
5	*Bemessungsfahrzeug*	7
	5.1 Fahrwege	7
	5.2 Parkfelder	7
6	*Abweichungen*	8
D	**Anordnung der Parkierungsanlagen und Parkfelder**	8
7	*Grundsätze*	8
8	*Parkieren ausserhalb des Strassenraumes*	8
	8.1 Anbindung an das Strassennetz	8
	8.2 Parkierungsanlagen	8
	8.3 Einzelgaragen	9
	8.4 Anlagen mit Veloabstellplätzen	10
9	*Parkieren innerhalb des Strassenraumes*	10
	9.1 Regeln für die Anordnung	10
	9.2 Längsparkierung	11
	9.3 Schräg- und Senkrechtparkierung	11
10	*Parkierungsformen*	12
	10.1 Längsparkierung	12
	10.2 Schrägparkierung	12
	10.3 Senkrechtparkierung	13
E	**Geometrie der Parkfelder und Fahrgassen**	14
11	*Geometrie der Längsparkfelder*	14
12	*Geometrie der Schräg- und Senkrechtparkfelder*	15
13	*Rollstuhlgerechte Parkfelder*	17
14	*Parkfelder für Kleinwagen*	18
15	*Parkfelder für Motorräder*	19
16	*Wände und Stützen*	22
17	*Vertikale Abmessungen*	23
18	*Quergefälle*	23
19	*Entwässerung der Verkehrsflächen*	23

TABLE DES MATIÈRES

		Page
A	**Généralités**	5
1	*Domaine d'application*	5
2	*Objet*	5
3	*But*	5
B	**Définitions**	5
4	*Définitions générales*	5
	4.1 Installation de stationnement	5
	4.2 Parking	5
	4.3 Garage individuel	5
	4.4 Aire de stationnement	5
	4.5 Case de stationnement	5
	4.6 Allée de circulation	6
	4.7 Voie de liaison	6
	4.8 Rampe	6
	4.9 Entrée et sortie	6
	4.10 Angle de stationnement	6
	4.11 Surface de débord	6
	4.12 Bordure de protection	6
C	**Conditions, exigences**	7
5	*Valeurs de référence des véhicules*	7
	5.1 Voies de liaison	7
	5.2 Cases de stationnement	7
6	*Dérogations*	8
D	**Disposition des installations et des cases de stationnement**	8
7	*Principes*	8
8	*Stationnement en dehors de l'espace routier*	8
	8.1 Liaison avec le réseau routier	8
	8.2 Installations de stationnement	8
	8.3 Garages individuels	9
	8.4 Installations avec stationnement de vélos	10
9	*Stationnement dans l'espace routier*	10
	9.1 Règles de disposition	10
	9.2 Stationnement longitudinal	11
	9.3 Stationnement oblique ou perpendiculaire	11
10	*Types de stationnement*	12
	10.1 Stationnement longitudinal	12
	10.2 Stationnement oblique	12
	10.3 Stationnement perpendiculaire	13
E	**Géométrie des cases de stationnement et des allées de circulation**	14
11	*Géométrie des cases de stationnement longitudinales*	14
12	*Géométrie des cases de stationnement obliques ou perpendiculaires*	15
13	*Cases de stationnement adaptées aux fauteuils roulants*	17
14	*Cases de stationnement pour petits véhicules*	18
15	*Cases de stationnement pour motocycles*	19
16	*Parois et piliers*	22
17	*Dimensions verticales*	23
18	*Dévers*	23
19	*Evacuation des eaux des surfaces de circulation*	23

© REGnorm

Licensed to: Nicolò Guffanti (vss@tramos.ch) / Downloaded 26.03.2026

F	**Geometrie der Zu- und Wegfahrtsanlagen**	24
20	*Fahrwege*	24
	20.1 Lichtraumprofil	24
	20.2 Lichte Höhe	26
	20.3 Schrammborde	26
	20.4 Kurvenverbreiterungen	26
	20.5 Längsneigung	29
	20.6 Änderung der Längsneigung	29
21	*Ein- und Ausfahrt mit Kontrolleinrichtungen*	30
22	*Ein- und Ausfahrt mit Toranlagen*	31
G	**Literaturverzeichnis**	32

F	**Géométrie des installations d'accès et de sortie**	24
20	*Voies de liaison*	24
	20.1 Gabarit d'espace libre	24
	20.2 Hauteur libre	26
	20.3 Bordures de protection	26
	20.4 Surlargeurs en courbe	26
	20.5 Déclivité	29
	20.6 Changement de déclivité	29
21	*Entrée et sortie avec dispositifs de contrôle*	30
22	*Entrée et sortie avec portes*	31
G	**Bibliographie**	32

© REGnorm

Licensed to: Nicolò Guffanti (vss@tramos.ch) / Downloaded 26.03.2026

A Allgemeines

1 Geltungsbereich

Diese Norm gilt für Parkierungsanlagen für Personenwagen und Motorräder. Sie gilt für öffentlich und nicht öffentlich zugängliche Parkierungsanlagen.

2 Gegenstand

Die Norm behandelt die Anordnung von Parkfeldern und die Geometrie aller Elemente von Parkierungsanlagen.

3 Zweck

Die Norm bietet für die Anordnung der Parkfelder sowie für die geometrische Bemessung von Parkierungsanlagen die Grundlagen, um

- die Betriebssicherheit der Parkierungsanlagen zu gewährleisten
- eine auf die Nutzung ausgerichtete Planung und Projektierung wirtschaftlicher Parkierungsanlagen zu ermöglichen
- Personenschäden sowie Schäden an Fahrzeugen und Bauteilen zu vermeiden
- eine angemessene Benutzerfreundlichkeit anzubieten

B Begriffe

4 Allgemeine Begriffe

4.1 Parkierungsanlage

Eine Parkierungsanlage ist eine Einrichtung, die dem Parkieren von Fahrzeugen des Individualverkehrs dient. Parkierungsanlagen sind Parkhäuser, Einzelgaragen, Parkplätze und Parkfelder im Strassenraum.

4.2 Parkhaus

Ein Parkhaus ist eine ein- oder mehrgeschossige, unter- oder oberirdische, teilweise oder vollständig gedeckte Parkierungsanlage.

4.3 Einzelgarage

Eine Einzelgarage ist eine gedeckte Parkierungsanlage für ein einzelnes Fahrzeug.

4.4 Parkplatz

Ein Parkplatz ist eine ebenerdige, ungedeckte Parkierungsanlage mit mehreren Parkfeldern.

4.5 Parkfeld

Ein Parkfeld ist eine abgegrenzte Fläche, auf der ein Fahrzeug parkiert werden darf.

A Généralités

1 Domaine d'application

Cette norme s'applique aux installations de stationnement pour les voitures de tourisme et les motocycles. Elle concerne les installations de stationnement accessibles ou non au public.

2 Objet

La norme traite de la disposition des cases de stationnement et de la géométrie de tous les éléments des installations de stationnement.

3 But

La norme fournit les bases pour la disposition des cases de stationnement ainsi que pour le dimensionnement géométrique des installations de stationnement afin de

- garantir la sécurité de l'exploitation des installations de stationnement
- permettre de planifier et d'établir des projets d'installations de stationnement économiques en fonction de leur affectation
- éviter des dommages corporels, aux véhicules et aux éléments de l'installation
- offrir une facilité d'usage appropriée

B Définitions

4 Définitions générales

4.1 Installation de stationnement

Une installation de stationnement est un ouvrage destiné au stationnement de véhicules de transport individuels, tels que parkings, garages individuels, aires et cases de stationnement dans l'espace routier.

4.2 Parking

Un parking est une installation de stationnement d'un ou plusieurs niveaux, partiellement ou totalement couverte, en sous-sol ou non.

4.3 Garage individuel

Un garage individuel est une installation de stationnement couverte pour un véhicule.

4.4 Aire de stationnement

Une aire de stationnement est une installation de stationnement en surface et à l'air libre comportant plusieurs cases de stationnement.

4.5 Case de stationnement

Une case de stationnement est une surface délimitée sur laquelle un véhicule est autorisé à stationner.

© REGnorm

Licensed to: Nicolò Guffanti (vss@tramos.ch) / Downloaded 26.03.2026

4.6 Fahrgasse

Eine Fahrgasse ist eine Verkehrsfläche neben den Parkfeldern für die Zu- und Wegfahrt sowie zum Manövrieren. Die Fahrgasse wird in der Regel auch von Fussgängern benützt.

4.7 Fahrweg

Ein Fahrweg ist eine Verkehrsfläche für Motorfahrzeuge ohne angrenzende Parkfelder. In der Regel werden die Fahrwege von Fussgängern nicht benützt.

4.8 Rampe

Eine Rampe ist ein Fahrweg zur Verbindung zwischen zwei Ebenen.

4.9 Einfahrt und Ausfahrt

Einfahrt und Ausfahrt sind die Fahrwegabschnitte am Rand der Parkierungsanlage, die mit Kontrolleinrichtungen, Schranken und Toranlagen ausgerüstet werden können.

4.10 Parkfeldwinkel

Der Parkfeldwinkel ist der Winkel zwischen den Längsachsen der Fahrgasse und des Parkfeldes.

4.11 Überhangstreifen

Ein Überhangstreifen ist ein Quer- oder Längsstreifen am Rande des Parkfeldes oder Fahrweges, der nur den Überhängen der Fahrzeuge Platz bieten muss, aber nicht mit Rädern befahren wird.

4.12 Schrammbord

Ein Schrammbord ist ein erhöhter Überhangstreifen an den Rändern der Fahrwege oder Fahrgassen, welcher die Berührung der begrenzenden Wände oder anderer Objekte mit der Karosserie der Fahrzeuge verhindern soll.

4.6 Allée de circulation

Une allée de circulation est une surface de circulation jouxtant les cases de stationnement, permettant d'y entrer, d'en sortir et de manœuvrer. En règle générale, les piétons utilisent aussi l'allée de circulation.

4.7 Voie de liaison

Une voie de liaison est une surface de circulation pour véhicules automobiles sans cases de stationnement avoisinantes. En règle générale, les piétons n'utilisent pas les voies de liaison.

4.8 Rampe

Une rampe est une voie de liaison entre deux niveaux.

4.9 Entrée et sortie

Une entrée ou une sortie est une partie de voie de liaison en limite de l'installation, pouvant être munie d'équipements de contrôle, de barrières ou de portes.

4.10 Angle de stationnement

L'angle de stationnement est l'angle formé par les axes longitudinaux de l'allée de circulation et de la case de stationnement.

4.11 Surface de débord

Une surface de débord est une bande transversale ou longitudinale en limite de la case de stationnement ou d'une voie de liaison offrant de l'espace uniquement aux porte-à-faux des véhicules, mais pas au passage de leurs roues.

4.12 Bordure de protection

Une bordure de protection est une surface de débord surélevée en limite des voies de liaison ou des allées de circulation servant à éviter le contact entre la carosserie des véhicules et les obstacles latéraux, par ex. parois ou autres objets.

© REGnorm

Licensed to: Nicolò Guffanti (vss@tramos.ch) / Downloaded 26.03.2026

C Voraussetzungen

5 *Bemessungsfahrzeug*

5.1 Fahrwege

Für die Festlegung der minimalen Abmessungen der Fahrwege wurde von folgenden Bemessungsfahrzeugdaten ausgegangen (siehe Tabellen 1 und 2).

C Conditions, exigences

5 *Valeurs de référence des véhicules*

5.1 Voies de liaison

Les dimensions minimales des voies de liaison sont déterminées par les valeurs de référence du dimensionnement des véhicules suivantes (voir tableaux 1 et 2).

Bemessungsfahrzeugdaten für die Festlegung der minimalen Abmessungen der Fahrwege ***Valeurs de référence des véhicules pour déterminer les dimensions minimales des voies de liaison***	
	Abmessung *Dimension* [m]
Breite der Fahrzeuge ohne Rückspiegel *Largeur des véhicules sans les rétroviseurs*	1,85[1)]
Maximaler Radstand *Empattement maximal*	3,10
Maximaler vorderer Überhang *Porte-à-faux avant maximal*	1,10
Minimal fahrbarer Wenderadius (Wand – Wand) *Rayon de courbure minimal (de paroi à paroi)*	6,80
Maximaler Überhang der Rückspiegel über die Fahrzeugräder *Porte-à-faux maximal des rétroviseurs par rapport aux roues du véhicule*	0,20

Tab. 1
Bemessungsfahrzeugdaten für die Festlegung der minimalen Abmessungen der Fahrwege

Tab. 1
Valeurs de référence des véhicules pour déterminer les dimensions minimales des voies de liaison

5.2 Parkfelder

Für die Abmessungen der Parkfelder sind folgende Bemessungsfahrzeugdaten massgebend.

5.2 Cases de stationnement

Le dimensionnement des cases de stationnement est déterminé à partir des valeurs de référence des véhicules suivantes.

Bemessungsfahrzeugdaten für die Festlegung der Abmessungen der Parkfelder ***Valeurs de référence des véhicules pour déterminer les dimensions des cases de stationnement***	
	Abmessung *Dimension* [m]
Breite der Fahrzeuge ohne Rückspiegel *Largeur des véhicules sans les rétroviseurs*	1,85[1)]
Minimaler seitlicher Platzbedarf für das Ein- und Aussteigen *Espace latéral minimal pour entrer dans le véhicule ou en sortir*	0,60
Länge des Fahrzeuges *Longueur du véhicule*	4,90[1)]

Tab. 2
Bemessungsfahrzeugdaten für die Festlegung der Abmessungen der Parkfelder

Tab. 2
Valeurs de référence des véhicules pour déterminer les dimensions des cases de stationnement

1) Bezogen auf den 2016 erschienenen Forschungsbericht Nr. 1569 «Geometrie des Fahrzeugparks der Schweiz» [14] decken die in Tabellen 1 und 2 aufgeführten Bemessungsgrössen der Fahrzeugbreiten und -längen rund 88% der zugelassenen Personenwagentypen ab.

1) Selon le rapport de recherche n° 1569 «Caractéristiques géométriques du parc de véhicules circulant en Suisse» paru en 2016 [14], les valeurs de dimensionnement concernant les largeurs et les longueurs de véhicules figurant dans les tableaux 1 et 2 couvrent environ 88% des types de voitures de tourisme admis.

© REGnorm

Licensed to: Nicolò Guffanti (vss@tramos.ch) / Downloaded 26.03.2026

6 Abweichungen

Die in dieser Norm angegebenen Abmessungen sind Mindestwerte. Falls es aus Gründen des Komforts erwünscht und wirtschaftlich tragbar ist, können einzelne Werte bei konkreten Projekten grösser gewählt werden.
Bei beengten Verhältnissen und bestehenden Situationen können unter Inkaufnahme der Komforteinbusse einzelne Werte geringfügig unterschritten werden. Die möglichen Unterschreitungen der Mindestwerte sind angegeben.

6 Dérogations

Les dimensions indiquées dans cette norme sont des valeurs minimales. Dans certains projets, pour autant que ce soit financièrement supportable, on peut pour des raisons de confort, opter pour des valeurs plus élevées.
Si l'espace est restreint et selon la situation, certaines valeurs peuvent être légèrement diminuées, avec pour corollaire une réduction du confort. Les diminutions possibles des valeurs minimales sont indiquées.

D Anordnung der Parkierungsanlagen und Parkfelder

7 Grundsätze

Bei der Anordnung der Parkierungsanlagen und Parkfelder sind folgende Grundsätze zu beachten

- Der Parkierungsverkehr darf den Verkehrsfluss des öffentlichen Strassennetzes nicht in unzumutbarer Weise behindern, insbesondere durch Manöver auf der Fahrbahn oder durch Rückstau bei Einfahrten.
- Der Parkierungsverkehr darf die Fussgänger und die Velofahrenden nicht gefährden und soll deren Komfort nicht unnötig verringern, beispielsweise durch Umwege.
- Für die Standortwahl und die Einfügung in die Umgebung sind die Grundsätze in VSS 40 280 «Parkieren; Grundlagen» [9] zu beachten.
- Für die Ermittlung des Angebots an Parkfeldern ist VSS 40 281 «Parkieren; Angebot an Parkfeldern für Personenwagen» [10] anzuwenden.
- Die Anordnung hat die Bedürfnisse von gehbehinderten Personen zu berücksichtigen. Diese Parkfelder sind leicht zugänglich, in der Nähe der Ein- und Ausgänge oder der Aufzüge anzuordnen. Es sind die SIA 500 «Hindernisfreie Bauten» [13] und die VSS 40 075 «Fussgängerverkehr; Hindernisfreier Verkehrsraum» (inklusive normativer Anhang) [3] zu beachten.

8 Parkieren ausserhalb des Strassenraumes

8.1 Anbindung an das Strassennetz

Die Anbindung an das Strassennetz ist gemäss VSS 40 050 «Grundstückzufahrten; Anordnung und Gestaltung» [1] zu gestalten.

8.2 Parkierungsanlagen

Organisationstypen von Parkierungsanlagen ausserhalb des Strassenraumes sind schematisch in Abbildung 1 dargestellt. In solchen Anlagen werden die Parkfelder in der Regel schräg oder senkrecht angeordnet. In gewissen Fällen sind auch Längsparkfelder möglich.

D Disposition des installations et des cases de stationnement

7 Principes

Les principes suivants seront respectés concernant la disposition des installations de stationnement et de leurs cases

- Le trafic induit par le stationnement ne doit pas gêner de manière exagérée celui du réseau routier public avoisinant, en particulier par des manœuvres sur la chaussée ou par des files d'attente à l'entrée.
- Le trafic induit par le stationnement ne doit pas mettre en danger les piétons et cyclistes et diminuer inutilement leur confort, par exemple par des détours.
- Les principes énoncés dans la VSS 40 280 «Stationnement; bases» [9] seront respectés lors du choix de l'emplacement et de l'insertion dans le voisinage.
- Pour la détermination de l'offre en cases de stationnement, la VSS 40 281 «Stationnement; offre en cases de stationnement pour les voitures de tourisme» [10] est à appliquer.
- La disposition tiendra compte des besoins des personnes à mobilité réduite. Les cases de stationnement qui leur sont destinées seront aisément accessibles et placées à proximité des accès ou des ascenseurs. On tiendra compte de la SIA 500 «Constructions sans obstacles» [13] et de la VSS 40 075 «Trafic piétonnier; espace de circulation sans obstacles» (y compris annexe normative) [3].

8 Stationnement en dehors de l'espace routier

8.1 Liaison avec le réseau routier

La liaison avec le réseau routier sera réalisée selon la VSS 40 050 «Accès riverains; disposition et aménagement» [1].

8.2 Installations de stationnement

Les divers types d'installations de stationnement en dehors de l'espace routier sont représentés schématiquement à la figure 1. En règle générale, sur de telles aires, les cases de stationnement sont disposées obliquement ou perpendiculairement. Dans certains cas, on peut également les disposer longitudinalement.

© REGnorm

Licensed to: Nicolò Guffanti (vss@tramos.ch) / Downloaded 26.03.2026

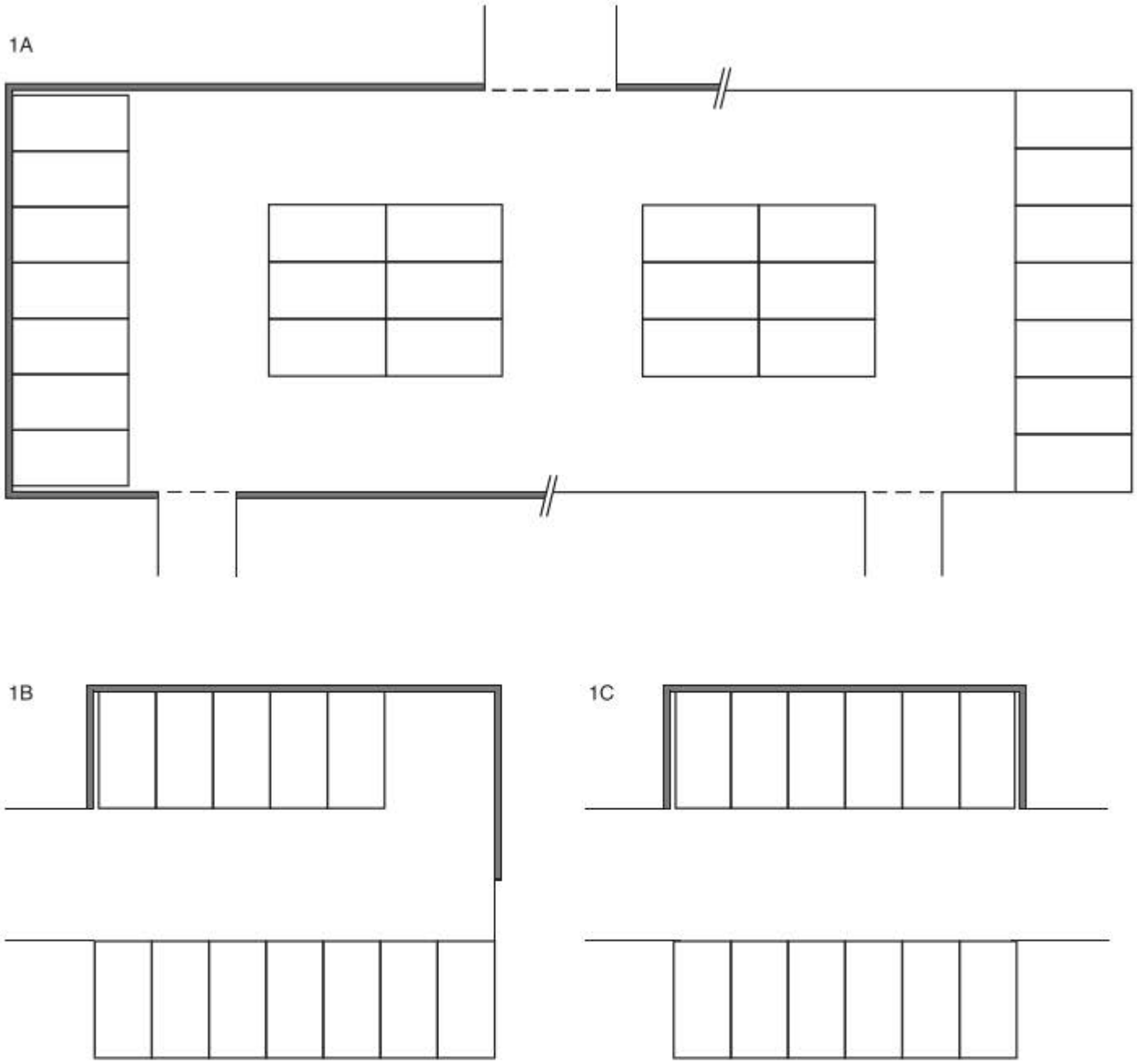

1A Parkierungsanlagen mit interner Zirkulation (Einbahnverkehr oder Gegenverkehr)
1B Parkierungsanlagen mit Sackgasse (nur Gegenverkehr möglich)
1C Parkierungsanlagen mit Durchfahrt (Einbahnverkehr oder Gegenverkehr)

Abb. 1
Mögliche Anordnungen von Parkierungsanlagen

1A Installations de stationnement avec circulation interne (sens unique ou bidirectionnel)
1B Installations de stationnement en impasse (uniquement bidirectionnel)
1C Installations de stationnement avec traversée (sens unique ou bidirectionnel)

Fig. 1
Dispositions possibles des installations de stationnement

8.3 Einzelgaragen

Einzelgaragen an öffentlichen Strassen sollen einen Vorplatz aufweisen, auf dem ein Fahrzeug abgestellt und gleichzeitig das Tor geöffnet werden kann, ohne dass der öffentliche Verkehrsraum beansprucht wird. In Ausnahmefällen, insbesondere aus Gründen des Ortsbildes oder an Strassen mit geringem Verkehrsaufkommen, kann von dieser Regel abgewichen werden.

8.3 Garages individuels

Une place doit être aménagée devant les garages individuels le long des routes publiques. Cette place doit permettre de parquer un véhicule pendant qu'on ouvre la porte du garage, ceci sans empiéter sur l'espace routier public. Dans des cas particuliers, pour des raisons de protection des sites ou si le volume de trafic est faible, on peut déroger à cette règle.

© REGnorm

Licensed to: Nicolò Guffanti (vss@tramos.ch) / Downloaded 26.03.2026

8.4 Anlagen mit Veloabstellplätzen

Für Parkierungsanlagen, in denen auch Velos abgestellt werden, sind folgende Grundsätze zu beachten

- Fahrwege von Motorfahrzeugen und Velos sollen getrennt geführt werden. Zu beachten sind dabei auch die unterschiedlichen Anforderungen bezüglich Rampenneigung und Lichtraumprofil.
- Die Abstellplätze für Velos müssen möglichst nahe beim Zielort angeordnet werden.
- In geschlossenen Parkhäusern sind die Langzeitparkfelder für Velos in einem baulich abgetrennten Raum anzuordnen.

Weitere Angaben für Velos sind in VSS 40 066 «Parkieren; Projektierung von Veloparkierungsanlagen» [2] enthalten.

9 Parkieren innerhalb des Strassenraumes

9.1 Regeln für die Anordnung

Parkierungsanlagen, deren Benutzung Manöver auf der Fahrbahn erfordern, sind in der Regel nur an siedlungsorientierten Strassen zulässig.
Die Parkfelder können auf oder neben der Fahrbahn angeordnet werden. Parkfelder neben der Fahrbahn sind für den Verkehrsfluss, die Sicherheit der Velos und Fussgängerquerungen günstiger. Parkfelder auf der Fahrbahn können als Verkehrsberuhigungselemente gemäss VSS 40 213 «Entwurf des Strassenraumes; Verkehrsberuhigungselemente» [6] dienen.

Die Wahl der Parkierungsform auf der Fahrbahn ist vor allem von den Platzverhältnissen abhängig. Die Breite der Fahrbahn wird durch den massgebenden Begegnungsfall und die Angaben in VSS 40 201 «Geometrisches Normalprofil; Grundabmessungen und Lichtraumprofil der Verkehrsteilnehmer» [4] sowie den Breiten gemäss den Tabellen 4, 5 und 6 bestimmt.
Im Bereich von Knoten und Grundstückszufahrten sind die Parkfelder so anzuordnen, dass die erforderlichen Sichtweiten gemäss VSS 40 273 «Knoten; Sichtverhältnisse in Knoten in einer Ebene» [8] eingehalten werden.

Hinweise zum Parkieren auf der Fahrbahn finden sich zudem in VSS 40 211 «Entwurf des Strassenraumes; Grundlagen» [5] und VSS 40 303 «Strassenprojektierung; Entwurf von Hauptverkehrsstrassen innerorts» [12].

Anordnungen von Parkfeldern mit Manövern auf der Fahrbahn sind in der Abbildung 2 dargestellt.

8.4 Installations avec stationnement de vélos

Pour les installations de stationnement accueillant aussi des vélos, les principes suivants seront respectés

- Les voies de liaison des véhicules automobiles devraient être distinctes de celles des vélos. Les différentes exigences relatives à la déclivité des rampes et au gabarit sont également à considérer.
- Les places de stationnement pour les vélos seront positionnées le plus près possible de la destination.
- Dans les parkings fermés, les cases de stationnement de longue durée pour les vélos seront prévues dans un local séparé.

D'autres indications concernant les vélos figurent dans la VSS 40 066 «Stationnement; conception des aménagements de stationnement pour vélos» [2].

9 Stationnement dans l'espace routier

9.1 Règles de disposition

Les installations de stationnement qui occasionnent des manœuvres sur la chaussée ne sont en général acceptables que sur des routes d'intérêt local.
Les cases de stationnement peuvent être disposées sur la chaussée ou à côté de celle-ci. Du point de vue de l'écoulement du flux de circulation, de la sécurité des vélos et des traversées pour les piétons, les cases de stationnement à côté de la chaussée sont plus favorables. Les cases de stationnement sur la chaussée peuvent servir d'éléments de modération du trafic selon la VSS 40 213 «Conception de l'espace routier; éléments de modération du trafic» [6].
Le choix du type de stationnement sur la chaussée dépend principalement de l'espace disponible. La largeur de la chaussée est déterminée en fonction du cas de croisement/dépassement déterminant et des indications de la VSS 40 201 «Profil géométrique type; dimensions de base et gabarit des usagers de la route» [4] ainsi que des largeurs figurant dans les tableaux 4, 5 et 6.
Dans les zones de carrefours et d'accès riverains, les cases de stationnement seront disposées de telle manière que les distances de visibilité nécessaires selon la VSS 40 273 «Carrefours; conditions de visibilité dans les carrefours à niveau» [8] soient respectées.
Des indications concernant le stationnement sur la chaussée figurent de plus dans la VSS 40 211 «Conception de l'espace routier; bases» [5] et la VSS 40 303 «Projets routiers; conception de routes principales à l'intérieur des localités» [12].
Les dispositions des cases de stationnement occasionnant des manœuvres sur la chaussée sont présentées à la figure 2.

© REGnorm

Licensed to: Nicolò Guffanti (vss@tramos.ch) / Downloaded 26.03.2026

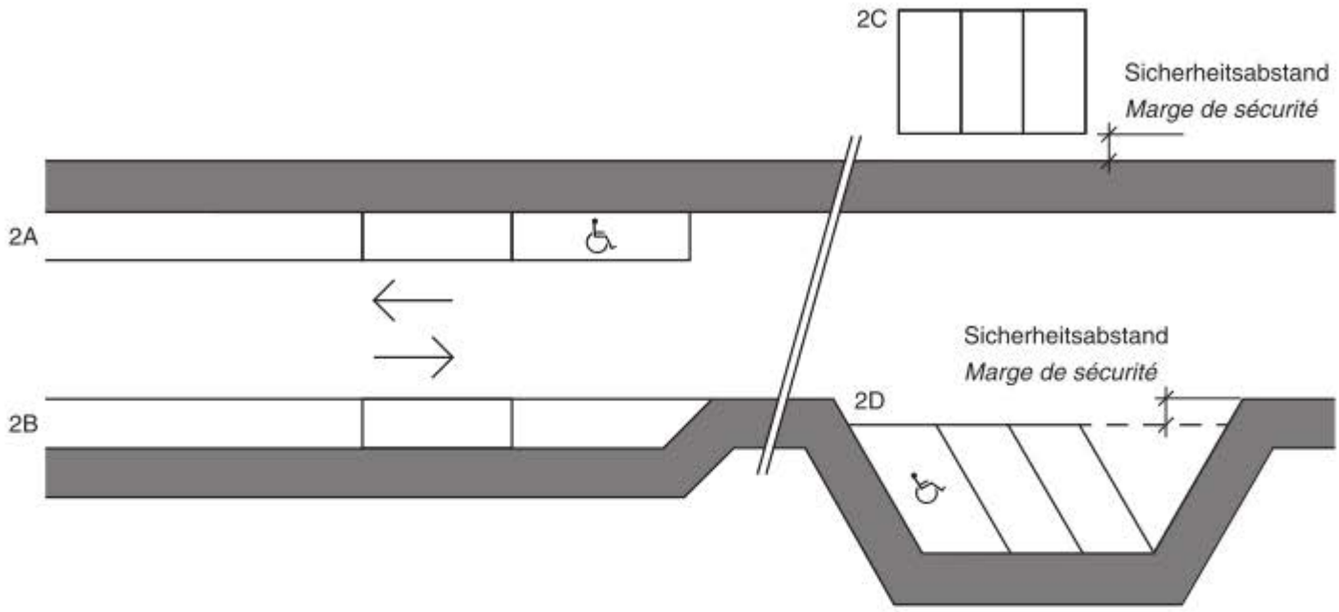

2A Längsparkfelder auf der Fahrbahn (mit oder ohne Unterteilung in einzelne Parkfelder)
2B Längsparkfelder ausserhalb der Fahrbahn (mit oder ohne Unterteilung in einzelne Parkfelder)
2C Schräg- oder Senkrechtparkfelder hinter dem Gehweg
2D Schräg- oder Senkrechtparkfelder vor dem Gehweg
Gehweg

Abb. 2
Anordnung von Parkfeldern mit Manövern auf der Fahrbahn von siedlungsorientierten Strassen

2A Cases de stationnement longitudinales sur la chaussée (avec ou sans marquage des cases)
2B Cases de stationnement longitudinales hors de la chaussée (avec ou sans marquage des cases)
2C Cases de stationnement obliques ou perpendiculaires derrière le trottoir
2D Cases de stationnement obliques ou perpendiculaires devant le trottoir
Trottoir

Fig. 2
Disposition des cases de stationnement occasionnant des manœuvres sur la chaussée des routes d'intérêt local

9.2 Längsparkierung

Längsparkfelder können gemäss Abbildung 2 auf (2A) oder ausserhalb der Fahrbahn (2B) angeordnet werden.

Bei Längsparkierung ist der Gehweg in der Regel hinter den Parkfeldern zu führen.

Den Konflikten beim Türöffnen ist entsprechend der Situation besondere Beachtung zu schenken.

9.3 Schräg- und Senkrechtparkierung

Schräg- und Senkrechtparkfelder sind normalerweise so anzulegen, dass vorwärts eingefahren wird. Schräg- und Senkrechtparkfelder können in siedlungsorientierten Strassen auch auf der Fahrbahn angeordnet werden.

Es ist anhand folgender Kriterien zu prüfen, ob der Gehweg gemäss Abbildung 2 hinter (2C) oder vor (2D) den Parkfeldern geführt wird
- Fussgängerfrequenz auf dem Gehweg
- Velofrequenz auf der Fahrbahn
- Umschlagshäufigkeit auf den Parkfeldern
- Publikumsnutzungen (Verkaufsläden, Dienstleistungsbetriebe) oder Schaufenster hinter den Parkfeldern

Dem Konfliktpotenzial und den Sichtverhältnissen für das Ausparkieren ist Rechnung zu tragen. Es ist ein Sicherheitsabstand zwischen den Schräg- und Senkrechtparkfeldern und der Fahrbahn oder dem Gehweg von mindestens 0,50 m einzuhalten.

9.2 Stationnement longitudinal

Selon la figure 2, les cases de stationnement longitudinales peuvent être disposées sur la chaussée (2A) ou hors de celle-ci (2B).
En règle générale, lorsque le stationnement est longitudinal, le trottoir doit être disposé derrière les cases de stationnement.
Selon la situation, on accordera une attention particulière aux conflits dûs à l'ouverture des portières.

9.3 Stationnement oblique ou perpendiculaire

Les cases de stationnement obliques ou perpendiculaires seront normalement disposées de manière à pouvoir y accéder en marche avant. Sur les routes d'intérêt local, les cases de stationnement obliques ou perpendiculaires peuvent également être disposées sur la chaussée.
Les critères suivants permettent d'examiner selon la figure 2 si le trottoir doit passer derrière (2C) ou devant (2D) les cases de stationnement
- importance du trafic piétonnier sur le trottoir
- importance du trafic cycliste sur la chaussée
- taux de rotation des cases de stationnement
- présence de magasins, de services ou de vitrines derrière les cases de stationnement

On tiendra compte des conflits potentiels et des conditions de visibilité. Une marge de sécurité d'au moins 0,50 m doit être respectée entre chaussée ou trottoir et cases de stationnement obliques ou perpendiculaires.

© REGnorm

Licensed to: Nicolò Guffanti (vss@tramos.ch) / Downloaded 26.03.2026

10 Parkierungsformen

Die Parkierungsformen werden mit dem Parkfeldwinkel in Bezug zur Fahrtrichtung definiert.

10.1 Längsparkierung

Die Längsanordnung erfolgt neben der Fahrspur parallel zur Fahrtrichtung (Parkfeldwinkel 0°).

10.2 Schrägparkierung

Die Schräganordnung (Parkfeldwinkel 30...75°) bedingt ein vorwärts Einparkieren und Einrichtungsverkehr in der Fahrgasse.
Die Schräganordnung erlaubt ein rasches Einparkieren und bewirkt eine geringere Belegung der Fahrgasse.

Je kleiner der Parkfeldwinkel, desto grösser werden die nicht nutzbaren Restflächen.
Bei der Schräganordnung gibt es – je nach Fahrtrichtung in den benachbarten Fahrgassen – zwei Betriebsarten (siehe Abbildung 3)

- Ist die Fahrtrichtung in benachbarten Fahrgassen entgegengerichtet, sind alle Parkfeldwinkel möglich.
- Ist die Fahrtrichtung in benachbarten Fahrgassen gleichgerichtet, ist ein Parkfeldwinkel von 45° optimal.

10 Types de stationnement

Les types de stationnement sont définis en fonction de l'angle de stationnement par rapport au sens de circulation.

10.1 Stationnement longitudinal

La disposition longitudinale à côté de la voie de circulation est parallèle au sens de circulation (angle de stationnement de 0°).

10.2 Stationnement oblique

La disposition oblique (angle de stationnement de 30...75°) nécessite l'entrée dans la case en marche avant et une allée de circulation à sens unique.
La disposition oblique permet d'entrer en marche avant rapidement et de limiter ainsi l'occupation des allées de circulation.
Plus l'angle de stationnement est petit, plus les surfaces résiduelles inutilisables sont conséquentes.
La disposition oblique présente deux types d'exploitation selon le sens de circulation dans les allées de circulation de part et d'autre des rangées de cases de stationnement (voir figure 3)

- Si le sens de circulation de l'allée adjacente est contraire, tous les angles de stationnement sont possibles.
- Si le sens de circulation est identique, un angle de stationnement de 45° est optimal.

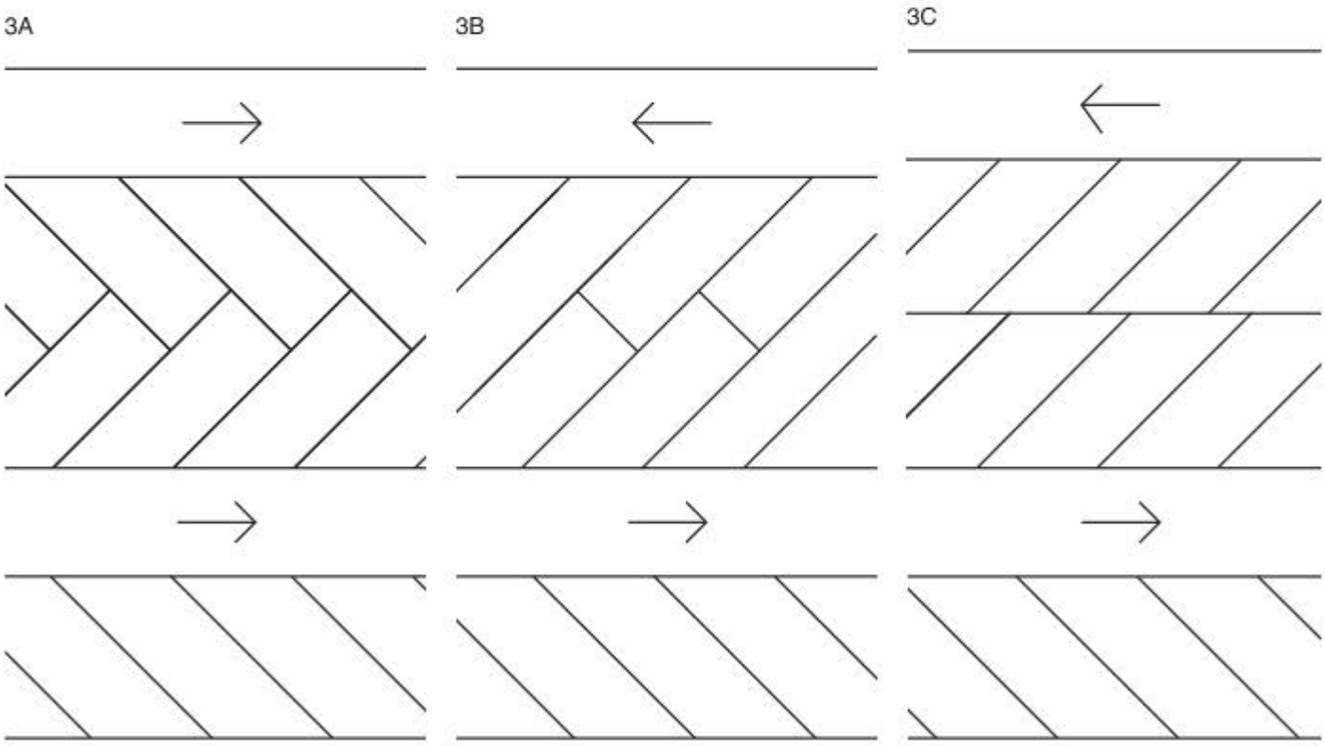

3A Schrägparkfelder mit gleichgerichteten Fahrtrichtungen, mit Verzahnung
3B Schrägparkfelder mit entgegengerichteten Fahrtrichtungen, mit Verzahnung
3C Schrägparkfelder mit entgegengerichteten Fahrtrichtungen, ohne Verzahnung

Abb. 3
Mögliche Verkehrsführungen bei Schrägparkierungen

3A Cases de stationnement obliques avec sens de circulation identiques et imbrication
3B Cases de stationnement obliques avec sens de circulation opposés et imbrication
3C Cases de stationnement obliques avec circulation à double sens, sans imbrication

Fig. 3
Sens de circulation possibles pour les cases de stationnement obliques

© REGnorm

Licensed to: Nicolò Guffanti (vss@tramos.ch) / Downloaded 26.03.2026

10.3 Senkrechtparkierung

Die Senkrechtanordnung (Parkfeldwinkel 90°) erlaubt Ein- oder Zweirichtungsverkehr in der Fahrgasse.

In Sackgassen mit senkrecht angeordneten Parkfeldern sind Manövrierflächen für das Ausparkieren aus den Parkfeldern am Sackgassenende zu berücksichtigen (siehe Abbildung 4 und Tabelle 3).
Weiter ist bei Sackgassen ohne Parkplatzzuordnungen die Notwendigkeit einer Wendemöglichkeit zu prüfen. Zum Beispiel kann für das Wendemanöver ein Endparkfeld freigehalten werden.

10.3 Stationnement perpendiculaire

La disposition perpendiculaire (angle de stationnement de 90°) permet une circulation à sens unique ou à double sens dans l'allée de circulation.
Dans les impasses, en cas de disposition perpendiculaire des cases de stationnement, on tiendra compte de surfaces de manœuvre pour la sortie des cases au bout de l'impasse (voir figure 4 et tableau 3).
Dans les impasses sans cases attribuées, la nécessité d'un espace supplémentaire pour le rebroussement est à examiner. Par exemple, la dernière case peut être laissée libre pour les manœuvres de rebroussement.

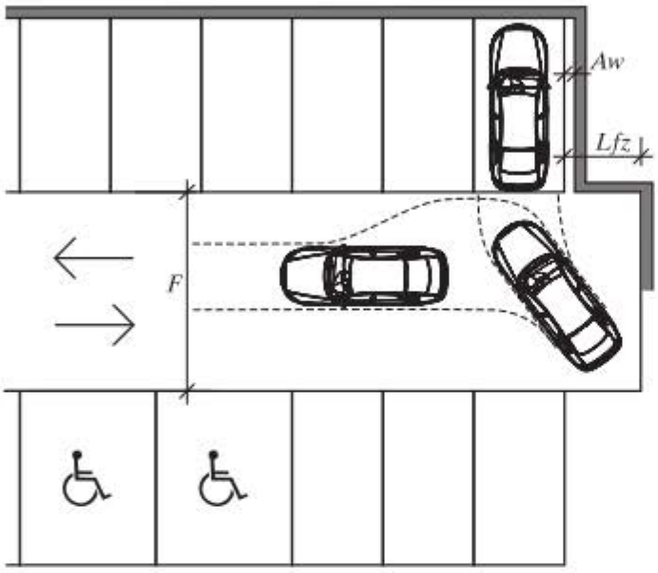

Aw Abstand zur Wand gemäss Ziffer 16
F Breite der Fahrgasse
Lfz Längenzuschlag Fahrgasse

Abb. 4
Mögliche Anordnung von Manövrierflächen für das Ausparkieren bei Parkierungsanlagen mit Sackgassen

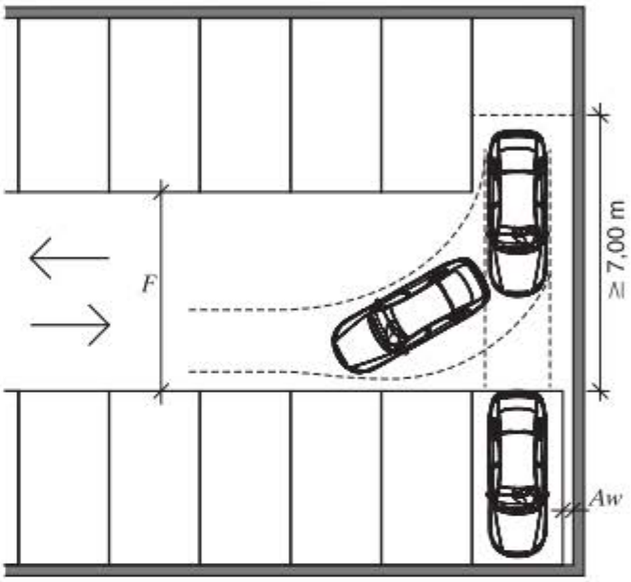

Aw Distance à une paroi selon chiffre 16
F Largeur de l'allée de circulation
Lfz Longueur additionnelle de l'allée de circulation

Fig. 4
Disposition possible des surfaces pour les manœuvres de sortie, dans les installations de stationnement en impasse

Längenzuschlag Fahrgasse in Sackgassen ***Longueur additionnelle de l'allée de circulation dans les impasses***	
Breite der Fahrgasse *Largeur de l'allée de circulation* *F* [m]	Längenzuschlag Fahrgasse *Longueur additionnelle de l'allée de circulation* *Lfz* [m]
6,50	1,50
6,00	1,75
5,50	2,00
5,00	2,25

Tab. 3
Längenzuschlag Fahrgasse in Sackgassen

Tab. 3
Longueur additionnelle de l'allée de circulation dans les impasses

© REGnorm

Licensed to: Nicolò Guffanti (vss@tramos.ch) / Downloaded 26.03.2026

E Geometrie der Parkfelder und Fahrgassen

11 *Geometrie der Längsparkfelder*

In Längsparkfelder wird normalerweise rückwärts eingefahren. Die Abmessungen sind in Abbildung 5 dargestellt.

E Géométrie des cases de stationnement et des allées de circulation

11 *Géométrie des cases de stationnement longitudinales*

L'entrée dans une case de stationnement longitudinale se fait normalement en marche arrière. Les dimensions sont représentées à la figure 5.

5A

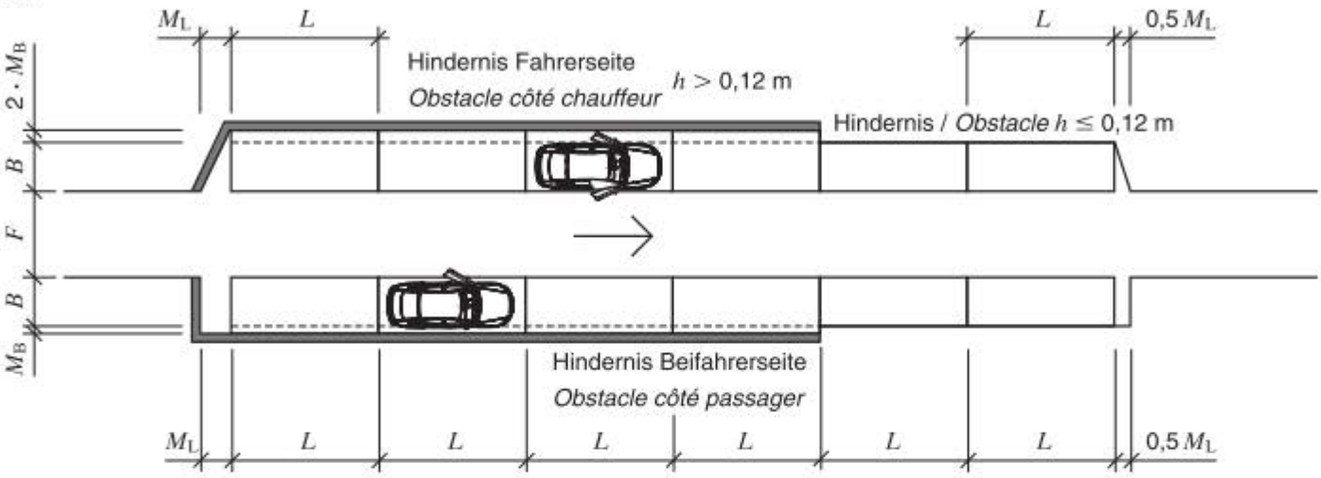

5B

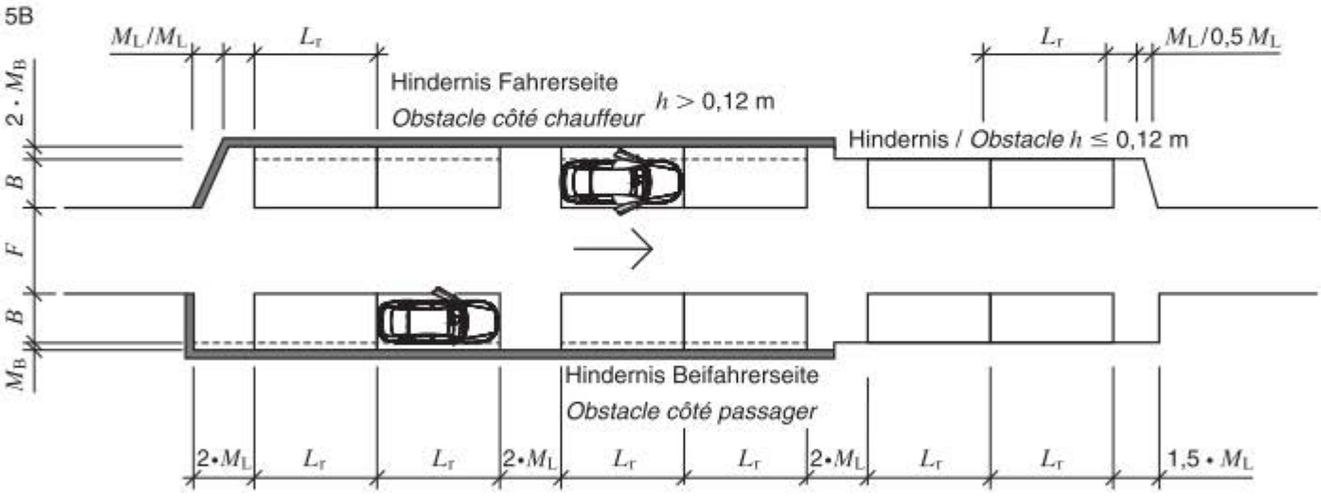

5A Anordnung mit Manövrierbereichen innerhalb Parkfelder
5B Anordnung mit Manövrierbereichen ausserhalb Parkfelder

F	Breite der Fahrgasse	3,50 m
B	Breite eines Parkfeldes	1,90 m
L	Länge eines Parkfeldes	6,00 m
L_r	Reduzierte Länge eines Parkfeldes	5,00 m
M_B	Manövrierzuschlag zur Breite	0,30 m
M_L	Manövrierzuschlag zur Länge	1,00 m

Abb. 5
Abmessungen der Längsparkfelder

5A Disposition avec des zones de manœuvre à l'intérieur des cases de stationnement
5B Disposition avec des zones de manœuvre à l'extérieur des cases de stationnement

F	Largeur de l'allée de circulation	3,50 m
B	Largeur d'une case de stationnement	1,90 m
L	Longueur d'une case de stationnement	6,00 m
L_r	Longueur réduite d'une case de stationnement	5,00 m
M_B	Largeur supplémentaire pour manœuvre	0,30 m
M_L	Longueur supplémentaire pour manœuvre	1,00 m

Fig. 5
Dimensions des cases de stationnement longitudinales

Bei markierten Parkfeldern beziehen sich die Abmessungen auf die Mitte der Markierungslinie.
Bei engen Platzverhältnissen und geringen Geschwindigkeiten kann die Breite F um maximal 0,20 m reduziert werden.
Auf Strassen mit einer Fahrbahnbreite von 5,00 m können im Ausnahmefall einzelne Längsparkfelder angeordnet wer-

Les dimensions des cases marquées correspondent au centre de la ligne de marquage.
Si l'espace à disposition est restreint et si les vitesses sont basses, la largeur F peut être réduite au maximum de 0,20 m.

Sur les routes d'une largeur de 5,00 m, on peut exceptionnellement disposer des cases longitudinales pour autant

© REGnorm

Licensed to: Nicolò Guffanti (vss@tramos.ch) / Downloaded 26.03.2026

den, falls die Fahrbahn an beiden Rändern nicht durch seitliche Hindernisse begrenzt wird.
Ist auf der Fahrbahn ein Radstreifen vorhanden, so ist ein Sicherheitsabstand von mindestens 0,70 m zwischen dem Radstreifen und den Längsparkfeldern anzuordnen.
Bei der Anordnung gemäss Abbildung 5B mit Manövrierbereichen ausserhalb Parkfelder kann mit einer Erhöhung des Manövrierzuschlags ML das Einparkieren zusätzlich erleichtert werden. Dies beschleunigt tendenziell den Manövriervorgang und kann zum Beispiel bei Längsparkfeldern mit hohen Umschlagsfrequenzen vorteilhaft sein.

12 *Geometrie der Schräg- und Senkrechtparkfelder*

In Schräg- und Senkrechtparkfelder wird in der Regel vorwärts eingefahren. Die Abmessungen für verschiedene Parkfeldwinkel sind in Abbildung 6 und in den Tabellen 4 und 5 enthalten.

que la chaussée ne soit pas limitée de chaque côté par des obstacles latéraux.
Une distance de sécurité d'au moins 0,70 m doit être prévue entre une bande cyclable et des cases de stationnement longitudinales.
Concernant la disposition selon la figure 5B impliquant des manœuvres à l'extérieur des cases de stationnement, l'insertion des véhicules peut être facilitée par une extension de la longueur ML. Les manœuvres sont alors plus rapides, un avantage pour les cases de stationnement longitudinales qui présentent un taux de rotation élevé.

12 *Géométrie des cases de stationnement obliques ou perpendiculaires*

L'entrée dans une case de stationnement oblique ou perpendiculaire se fait normalement en marche avant. Les dimensions pour différents angles de stationnement sont indiquées à la figure 6 et aux tableaux 4 et 5.

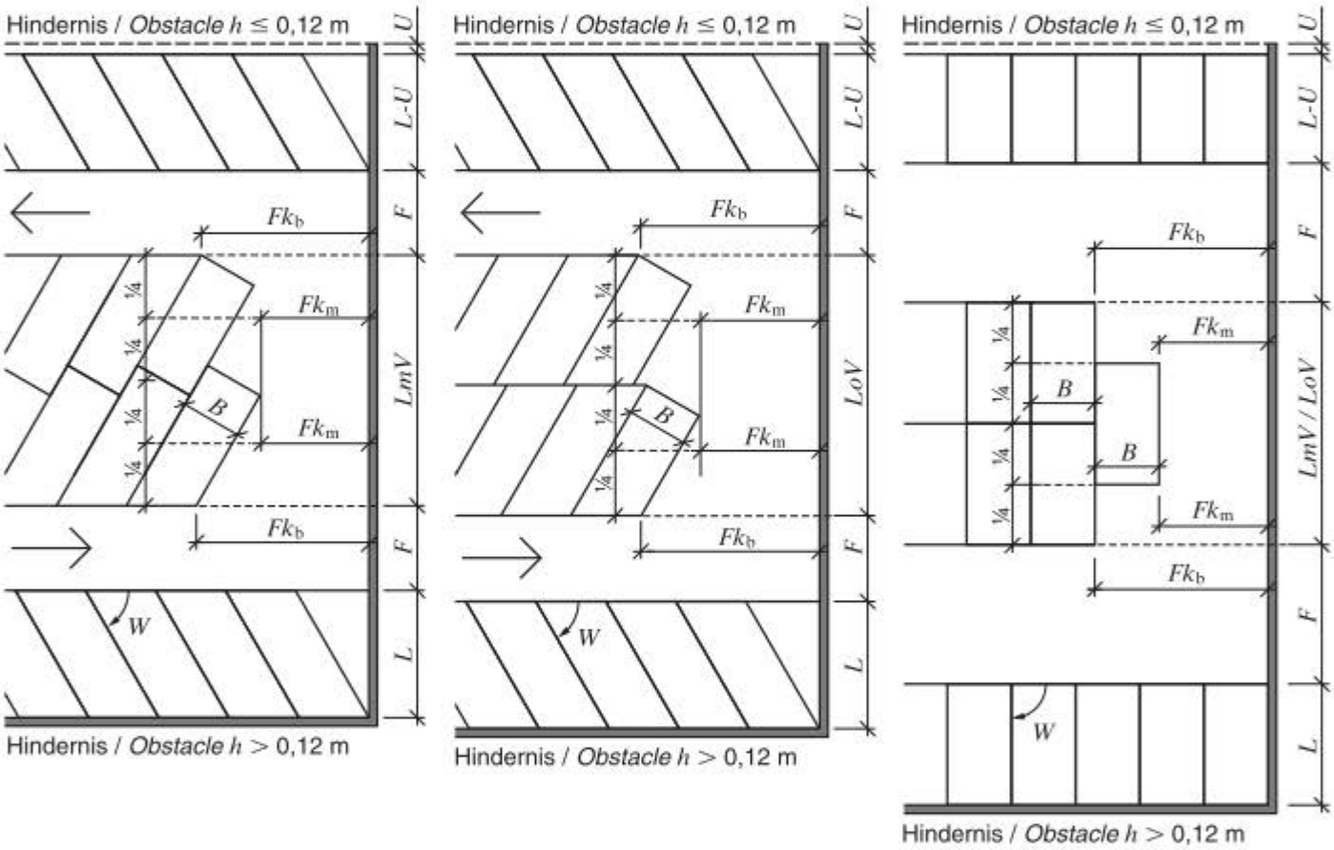

W	Parkfeldwinkel
F	Fahrgassenbreite in Geraden
Fk_b	Fahrgassenbreite in Kehren, Bogenanfang, -ende
Fk_m	Fahrgassenbreite in Kehren, Mittelteil
B	Breite eines Parkfeldes (senkrecht zur Längsausrichtung)
L	Länge eines Parkfeldes
LmV	Länge zweier aneinander stossende Parkfelder mit Verzahnung
LoV	Länge zweier aneinander stossende Parkfelder ohne Verzahnung
U	Breite des Überhangstreifens

Abb. 6
Abmessungen der Schräg- und Senkrechtparkfelder

W	Angle de stationnement
F	Largeur des allées de circulation en alignement
Fk_b	Largeur des allées de circulation dans les courbes, début et fin de la courbe
Fk_m	Largeur des allées de circulation dans les courbes, section intermédiaire
B	Largeur d'une case de stationnement (perpendiculaire au marquage de case en longueur)
L	Longueur d'une case de stationnement
LmV	Longueur de deux cases de stationnement accolées avec imbrication
LoV	Longueur de deux cases de stationnement accolées sans imbrication
U	Largeur du débord

Fig. 6
Dimensions des cases de stationnement obliques ou perpendiculaires

© REGnorm

Licensed to: Nicolò Guffanti (vss@tramos.ch) / Downloaded 26.03.2026

Abmessungen der Schräg- und Senkrechtparkfelder *Dimensions des cases de stationnement obliques ou perpendiculaires*						
Parkfeld-winkel *Angle de stationnement* W	Breite der Fahrgasse *Largeur de l'allée de circulation* F [m]	Breite des Parkfeldes *Largeur de la case de stationnement* B [m]	Länge des Parkfeldes *Longueur de la case de stationnement* L [m]	LmV [m]	LoV [m]	Breite des Überhang-streifens *Largeur du débord* U [m]
90°	6,50 6,25 6,00 5,75 5,50 5,25 5,00	2,50 2,55 2,60 2,65 2,70 2,75 2,80	5,00	10,00		0,50
75°	5,00 4,50	2,50 2,65	5,30	10,20	10,40	0,50
70°	4,50 4,00	2,50 2,70	5,30	10,00	10,30	0,50
60°	3,50 3,20	2,50 2,80	5,25	9,50	10,00	0,45
45°	3,20	2,50	4,80	8,60	9,10	0,35
30°	3,20	2,50	4,10	6,50	8,20	0,25

Tab. 4
Abmessungen der Schräg- und Senkrechtparkfelder

Tab. 4
Dimensions des cases de stationnement obliques ou perpendiculaires

Die Abstände zu Wänden und Stützen werden in Ziffer 16 (Wände und Stützen) behandelt.
Zwischenmasse von Fahrgassenbreiten und/oder Parkfeldbreiten sowie Parkfeldwinkeln können linear interpoliert werden.
Die in Tabelle 4 angegebenen Werte zur Fahrgassenbreite F beziehen sich auf den Platzbedarf für das Ein- und Ausparkieren, unabhängig des Verkehrsregimes.

Bei Parkierungsanlagen mit hohen Umschlagsfrequenzen je Parkfeld kann zur Komfortverbesserung die Parkfeldbreite B um 0,10 m erhöht werden. Weiter besteht auch die Möglichkeit, ein entsprechendes Verhältnis von Parkfeldbreite und Fahrgasse zu wählen.

Bei engen Platzverhältnissen aufgrund der Rahmenbedingungen (z.B. bestehende Bauten und Anlagen) kann die Parkfeldbreite B um 0,10 m reduziert werden. Die Reduktion bewirkt aber eine entsprechende Komforteinbusse. Für Parkfelder mit hohen Umschlagsfrequenzen ist eine Reduktion der Parkfeldbreite B nicht empfehlenswert.
Bei Parkierungsanlagen mit hohen Fussgängerfrequenzen in den Fahrgassen ist die Fussgängerführung besonders zu beachten. Je nach Benutzerbedürfnissen (Fussgänger, Fussgänger mit Einkaufswagen usw.) und Komfortansprüchen sollen die Fahrgassenbreiten erhöht werden. Dazu empfiehlt sich ein Zuschlag von mindestens 0,80 m zu den Werten von Tabelle 5. Betreffend der Fussgängerführung in Parkierungsanlagen gelten weiter die Empfehlungen der VSS 40 292 «Parkieren; Gestaltung und Ausrüstung der Parkierungsanlagen» [11].

Les distances par rapport aux parois et aux piliers sont traitées sous chiffre 16 (parois et piliers).
Les largeurs d'allées de circulation et/ou de cases de stationnement pour des valeurs d'angles intermédiaires peuvent être interpolées linéairement.
Les valeurs indiquées dans le tableau 4 pour la largeur des allées de circulation F se rapportent à la place nécessaire pour entrer sur la case et en sortir, indépendamment du régime de circulation.
Dans les installations de stationnement où le taux de rotation par case est élevé, la largeur des cases de stationnement B peut être augmentée de 0,10 m afin d'améliorer le confort. Il est aussi possible d'opter pour un autre rapport déterminé entre largeur de case de stationnement et allée de circulation.
Dans le cas où l'espace disponible est restreint en raison d'aménagements existants, la largeur B de la case de stationnement peut être réduite de 0,10 m. Cette réduction implique toutefois une diminution du confort. Il n'est pas recommandé de réduire la largeur B pour les cases de stationnement qui présentent un taux d'utilisation élevé.
Dans les installations de stationnement à fort trafic piétonnier sur les allées de circulation, on prêtera une attention particulière au guidage des piétons. En fonction des besoins des usagers (piétons, piétons avec chariot, etc.) et des exigences en matière de confort, il y a lieu d'augmenter la largeur des allées de circulation. Dans ce cas un supplément d'au moins 0,80 m est recommandé par rapport aux valeurs du tableau 5. De plus, en ce qui concerne le guidage des piétons dans les installations de stationnement, les recommandations de la VSS 40 292 «Stationnement; conception et équipement des installations de stationnement» [11] s'appliquent.

© REGnorm

Licensed to: Nicolò Guffanti (vss@tramos.ch) / Downloaded 26.03.2026

Breiten der Fahrgassen in Geraden und Kehren ***Largeur des allées de circulation en alignement et en courbe***			
Verkehrsregime *Régime de circulation*	Breite in Geraden *Largeur en alignement* F [m]	Breite in Kehren *Largeur en courbe* Fk_m [m]	 Fk_b [m]
Einbahnverkehr *Trafic à sens unique*	3,20	4,00	7,50
Gegenverkehr *Trafic bidirectionnel*	5,50	6,50	9,00

Tab. 5
Breiten der Fahrgassen in Geraden und Kehren

Tab. 5
Largeurs des allées de circulation en alignement et en courbe

Die Breiten gemäss Tabelle 5 stellen das Befahren einzelner Abschnitte der Parkierungsanlage im Einbahn- oder Gegenverkehr sicher. Weiter sind die Anforderungen für Kurvenverbreiterungen gemäss Ziffer 20.4 zu beachten. Kehren mit einem Aussenradius von weniger als 7,50 m sind zu vermeiden (siehe Tabelle 11).

Bei Parkierungsanlagen mit Gegenverkehrsregime und geringem Verkehrsaufkommen kann die in Tabelle 5 angegebene Fahrgassenbreite um maximal 0,50 m reduziert werden. Die Anforderungen gemäss Tabelle 4 sind jedoch einzuhalten. Die Reduktion der Fahrgassenbreite bewirkt eine Komforteinbusse und erfordert entsprechend tiefe Geschwindigkeiten beim Kreuzen.

13 Rollstuhlgerechte Parkfelder

Rollstuhlgerechte Parkfelder sind gemäss Anforderungen der VSS 40 075 [3] auszuführen und mit dem Rollstuhl-Signet zu kennzeichnen.

Sie sind möglichst nahe bei den hindernisfreien Zugängen anzuordnen.
Schräg- oder Senkrechtparkfelder haben eine Breite von 3,50 m. Ist links neben dem Parkfeld auf der gesamten Länge des Parkfeldes ein mindestens 1,00 m breiter niveaugleicher und freier Bereich vorhanden, so kann das Parkfeld auf 2,50 m reduziert werden. Die Länge eines Parkfeldes richtet sich nach den Angaben von Tabelle 4 und Abbildung 7.

Längsparkfelder sind 8,00 m lang. Das Parkfeld kann auch kürzer sein, wenn hinter dem Parkfeld (Fahrzeugheck) ein entsprechender freier Bereich vorhanden ist. Bezüglich der Parkfeldbreite gelten die Normbreiten gemäss Abbildung 5. Es ist jedoch zumindest fahrerseitig eine Ein- und Aussteigezone von 1,40 m Breite zu gewährleisten, die möglichst niveaugleich sein sollte. In verkehrsorientierten Strassen sollte die Ein- und Aussteigezone ausserhalb der Fahrspuren liegen.

Les largeurs données dans le tableau 5 garantissent la circulation sur chaque tronçon des allées de circulation de l'installation de stationnement dans un seul sens ou en bidirectionnel. De plus, on tiendra compte des exigences en matière de surlargeur dans les courbes selon le chiffre 20.4. On évitera les courbes d'un rayon extérieur de moins de 7,50 m (voir tableau 11).
Dans les installations de stationnement où le régime de circulation est bidirectionnel et si le volume de trafic est faible, la largeur de l'allée de circulation donnée dans le tableau 5 peut être réduite de 0,50 m au maximum. Les exigences du tableau 4 doivent toutefois être respectées. La réduction de la largeur des allées de circulation occasionne une diminution du confort. Les croisements doivent donc être faits à vitesse réduite.

13 Cases de stationnement adaptées aux fauteuils roulants

Les cases de stationnement adaptées aux fauteuils roulants doivent être conçues conformément aux exigences de la VSS 40 075 [3] et signalées avec le symbole «fauteuil roulant».
Les cases sont à placer au plus près des accès sans obstacles.
Les cases de stationnement obliques ou perpendiculaires auront une largeur de 3,50 m. S'il y a à gauche de la case et sur toute sa longueur un espace d'au moins 1,00 m de large au même niveau, alors la largeur de la case peut être réduite à 2,50 m. La longueur d'une case sera conforme aux indications du tableau 4 et de la figure 7.

Les cases de stationnement longitudinales auront une longueur de 8,00 m. La case peut aussi être plus courte, à condition qu'il y ait derrière la case un espace libre correspondant (dispositif de chargement arrière). En ce qui concerne les largeurs des cases de stationnement, les largeurs normalisées selon la figure 5 sont applicables. Toutefois, côté conducteur, un espace d'au moins 1,40 m de large doit être à disposition pour entrer et sortir du véhicule. Cet espace doit si possible être à niveau. Sur les routes à orientation trafic, la zone d'entrée et de sortie du véhicule devrait être située en dehors des voies de circulation.

© REGnorm

Licensed to: Nicolò Guffanti (vss@tramos.ch) / Downloaded 26.03.2026

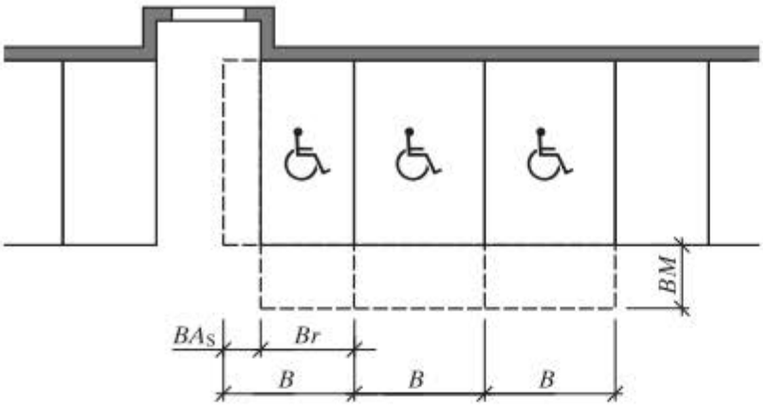

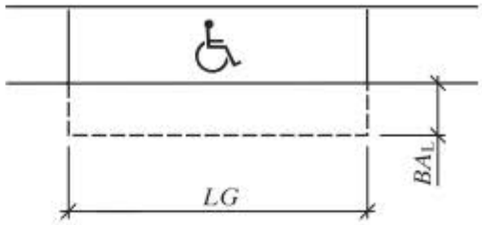

B	Breite eines Schräg- oder Senkrechtparkfeldes (senkrecht zur Längsausrichtung)	3,50 m
Br	Reduzierte Breite eines Schräg- oder Senkrechtparkfeldes (senkrecht zur Längsausrichtung)	2,50 m
BA_S	Seitliche Ein- und Aussteigezone eines reduzierten Parkfeldes (z.B. bei Durchgängen)	1,00 m
BM	Ein- und Ausladezone	1,70 m
BA_L	Ein- und Aussteigezone eines Längsparkfeldes	1,40 m
LG	Länge eines Längsparkfeldes (inkl. Ein- und Ausladezone)	8,00 m

Abb. 7
Abmessungen der Parkfelder für Fahrzeuge von gehbehinderten Personen

B	Largeur d'une case de stationnement oblique ou perpendiculaire (perpendiculaire au marquage de case en longueur)	3,50 m
Br	Largeur réduite d'une case de stationnement oblique ou perpendiculaire (perpendiculaire au marquage de case en longueur)	2,50 m
BA_S	Zone latérale d'entrée et de sortie du véhicule pour une case de stationnement réduite (p.ex. en raison d'un accès)	1,00 m
BM	Zone de chargement et de déchargement	1,70 m
BA_L	Zone d'entrée et de sortie du véhicule pour une case longitudinale	1,40 m
LG	Longueur d'une case longitudinale (y compris zone de chargement et de déchargement)	8,00 m

Fig. 7
Dimensions des cases de stationnement pour véhicules de personnes à mobilité réduite

14 Parkfelder für Kleinwagen

Um Fläche zu sparen und um Restflächen auszunützen, können Parkfelder für Kleinwagen angeordnet werden, welche die Standardabmessungen gemäss Ziffern 11 und 12 unterschreiten.
Die Mindestmasse für Kleinwagenparkfelder werden durch das Minimalfahrzeug (Länge 2,50 m, Breite 1,55 m, Wenderadius 4,35 m) bestimmt und sind in den Tabellen 6 und 7 angegeben.

14 Cases de stationnement pour petits véhicules

Afin d'économiser de l'espace et d'utiliser les surfaces résiduelles, des cases de stationnement pour petits véhicules peuvent être prévues. Leurs dimensions sont plus petites que celles des standards donnés sous chiffres 11 et 12.
Les dimensions minimales des cases de stationnement pour petits véhicules sont déterminées en fonction du véhicule minimal (longueur 2,50 m, largeur 1,55 m, rayon de braquage 4,35 m). Elles figurent aux tableaux 6 et 7.

Abmessungen der Längsparkfelder für Kleinwagen
Dimensions des cases de stationnement longitudinales pour petits véhicules

Breite der Fahrgasse *Largeur de l'allée de circulation* F [m]	Breite des Parkfeldes *Largeur de la case de stationnement* B [m]	Länge des Parkfeldes *Longueur de la case de stationnement* L [m]	Reduzierte Länge des Parkfeldes *Longueur réduite de la case de stationnement* L_r [m]	Manövrierzuschlag zur Breite des Parkfeldes *Supplément de manœuvre en largeur de la case de stationnement* M_B [m]	Manövrierzuschlag zur Länge des Parkfeldes *Supplément de manœuvre en longueur de la case de stationnement* M_L [m]
3,00	1,80	3,70	2,80	0,20	0,90

Tab. 6
Abmessungen der Längsparkfelder für Kleinwagen

Tab. 6
Dimensions des cases de stationnement longitudinales pour petits véhicules

© REGnorm

Licensed to: Nicolò Guffanti (vss@tramos.ch) / Downloaded 26.03.2026

Abmessungen der Schräg- und Senkrechtparkfelder für Kleinwagen *Dimensions des cases de stationnement obliques ou perpendiculaires pour petits véhicules*					
Parkfeld-winkel *Angle de stationnement* *W*	Breite der Fahrgasse *Largeur de l'allée de circulation* *F* [m]	Breite des Parkfeldes *Largeur de la case de stationnement* *B* [m]	Länge des Parkfeldes *Longueur de la case de stationnement* *L* [m]	*LmV* [m]	*LoV* [m]
90°	4,20 3,20	2,25 2,40	2,80	5,60	5,60
75°	3,20 3,00	2,25 2,40	3,10	5,80	6,00
60°	3,00	2,25	3,20	5,60	6,00

Tab. 7
Abmessungen der Schräg- und Senkrechtparkfelder für Kleinwagen

Tab. 7
Dimensions des cases de stationnement obliques ou perpendiculaires pour petits véhicules

Breiten der Fahrgassen in Geraden und Kehren für Kleinwagen *Largeurs des allées de circulation pour petits véhicules, en alignement et en courbe*			
Verkehrsregime *Régime de circulation*	Breite in Geraden *Largeur en alignement* *F* [m]	Breite in Kehren *Largeur en courbe* Fk_m [m]	Fk_b [m]
Einbahnverkehr *Trafic à sens unique*	3,00	3,50	4,50
Gegenverkehr *Trafic bidirectionnel*	4,60	5,00	7,25

Tab. 8
Breiten der Fahrgassen in Geraden und Kehren für Kleinwagen

Tab. 8
Largeurs des allées de circulation pour petits véhicules, en alignement et en courbe

Betreffend der Zwischenmasse, Minder- und Mehrbreiten gelten die entsprechenden Angaben in Ziffer 12.
Die Breiten gemäss Tabelle 8 stellen das Befahren einzelner Abschnitte der Parkierungsanlage im Einbahn- oder Gegenverkehr sicher. Bei Parkfeldanordnungen, die in Kehren einen Aussenradius von weniger als 5,00 m ergeben, ist die fahrgeometrische Befahrbarkeit nachzuweisen. Bei hohen Fussgängerfrequenzen ist ein Zuschlag gemäss den entsprechenden Angaben in Ziffer 12 zu empfehlen.

Concernant les valeurs intermédiaires, largeurs inférieures ou surlargeurs, les indications au chiffre 12 s'appliquent.
Les largeurs données dans le tableau 8 garantissent la circulation sur chaque tronçon des allées de circulation de l'installation de stationnement dans un seul sens ou en bidirectionnel. Dans le cas où la disposition des cases de stationnement implique une courbe avec un rayon extérieur de moins de 5,00 m, il est nécessaire de contrôler la giration de la manœuvre. Si le trafic piétonnier est élevé, un supplément conforme aux indications selon le chiffre 12 est recommandé.

15 Parkfelder für Motorräder

Die Abmessungen für Motorradparkfelder sind in Abbildung 8 und Tabelle 9 enthalten.
Die Parkplatzmarkierung kann mit oder ohne Unterteilung in einzelne Parkfelder erfolgen.

15 Cases de stationnement pour motocycles

Les dimensions des cases de stationnement pour motocycles sont indiquées à la figure 8 et au tableau 9.
Le marquage des places de stationnement peut être fait avec ou sans subdivision en cases individuelles.

© REGnorm

Licensed to: Nicolò Guffanti (vss@tramos.ch) / Downloaded 26.03.2026

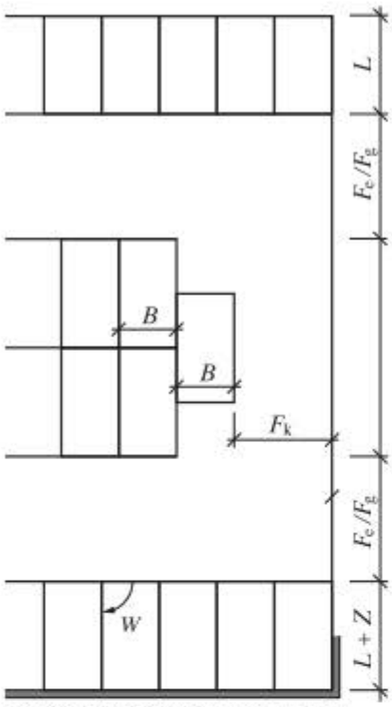

Hindernis / *Obstacle h* > 0,12 m

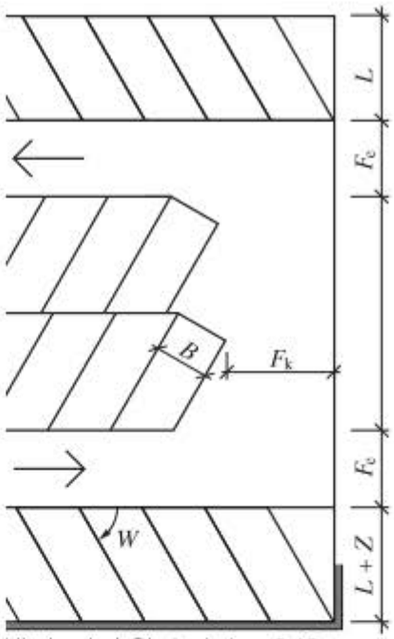

Hindernis / *Obstacle h* > 0,12 m

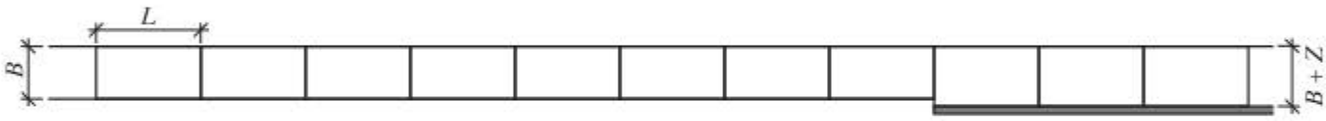

W	Parkfeldwinkel
F_e	Breite der Fahrgasse im Einbahnverkehr
F_g	Breite der Fahrgasse im Gegenverkehr
F_k	Breite der Fahrgasse in Kehren
B	Breite eines Parkfeldes (senkrecht zur Längsausrichtung)
L	Länge des Parkfeldes
Z	Zuschlag bei Hindernissen (Wände)

Abb. 8
Abmessungen [m] der Parkfelder für Motorräder

W	Angle de stationnement
F_e	Largeur de l'allée de circulation à sens unique
F_g	Largeur de l'allée de circulation à trafic bidirectionnel
F_k	Largeur des allées de circulation dans les courbes
B	Largeur d'une case de stationnement (perpendiculaire au marquage de case en longueur)
L	Longueur de la case de stationnement
Z	Supplément en cas d'obstacle (parois)

Fig. 8
Dimensions [m] des cases de stationnement pour motocycles

Seitlichen Hindernissen mit einer Höhe von mehr als 0,12 m ist Rechnung zu tragen (Stützen, Wände und Leitungsinstallationen). Die Einhaltung eines Abstandes von 0,20 m zu seitlichen Hindernissen wird empfohlen.

On tiendra compte des obstacles latéraux (piliers, parois, conduites) d'une hauteur supérieure à 0,12 m. Il est recommandé de respecter une distance de 0,20 m par rapport aux obstacles latéraux.

© REGnorm

Licensed to: Nicolò Guffanti (vss@tramos.ch) / Downloaded 26.03.2026

Abmessungen der Parkfelder für Motorräder ***Dimensions des cases de stationnement pour motocycles***						
Parkfeld-winkel *Angle de stationnement* W	Breite des Parkfeldes *Largeur de la case de stationne-ment* B [m]	Länge des Parkfeldes *Longueur de la case de stationne-ment* L [m]	Zuschlag bei Hindernissen (Wände) *Supplément en cas d'obs-tacle (parois)* Z [m]	Breite der Fahrgasse im Einbahn-verkehr *Largeur de l'allée de circulation à sens unique* F_e [m]	Breite der Fahrgasse im Gegen-verkehr *Largeur de l'allée de circulation à trafic bidirectionnel* F_g [m]	Breite der Fahrgasse in Kehren (ohne Kreuzen) *Largeur de l'allée de circulation en courbe (sans croisement)* F_k [m]
90°	1,20	2,30	0,20	3,00	4,00	2,50
60°	1,20	2,10	0,10	2,50	–	2,75
45°	1,20	1,90	0,05	2,00	–	3,00
30°	1,20	1,70	–	2,00	–	3,00
0° (längs / *longitudinal*)	1,20	2,50	0,20	2,00	4,00	3,00

Tab. 9
Abmessungen der Parkfelder für Motorräder

Tab. 9
Dimensions des cases de stationnement pour motocycles

© REGnorm

Licensed to: Nicolò Guffanti (vss@tramos.ch) / Downloaded 26.03.2026

16 Wände und Stützen

Für Längsparkfelder sind die erforderlichen Abstände zu seitlichen Hindernissen in Ziffer 11, Abbildung 5 enthalten.

Für Schräg- und Senkrechtparkfelder sind die Abstände zu seitlichen Bauteilen wie Wänden, Zäune, Stützen usw. in der Abbildung 9 und der Tabelle 10 definiert.

16 Parois et piliers

Concernant les cases de stationnement longitudinales, les distances nécessaires par rapport aux obstacles sont indiquées au chiffre 11 à la figure 5.
Concernant les cases de stationnement obliques ou perpendiculaires, les distances par rapport aux parties de construction telles que parois, clôtures, piliers, etc. sont données à la figure 9 et au tableau 10.

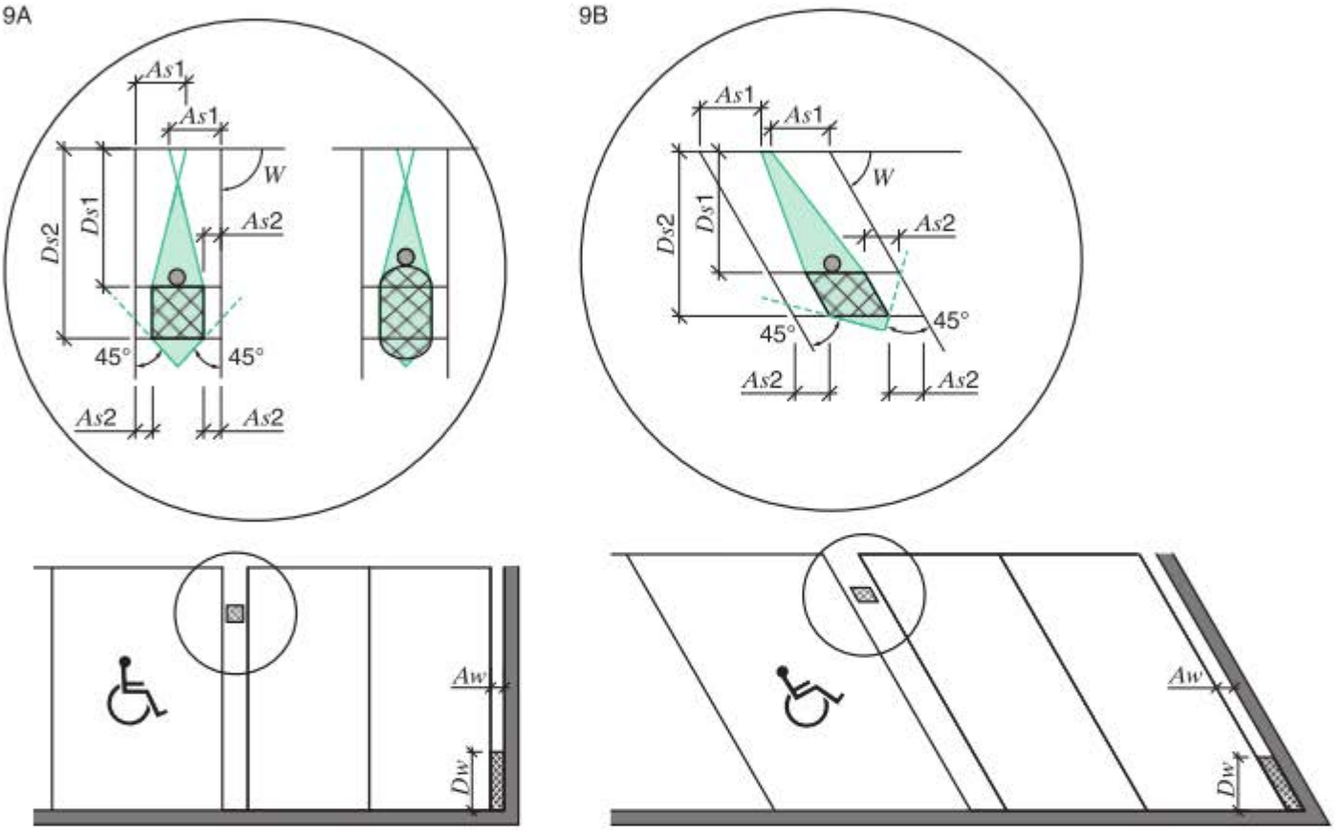

9A Anordnung bei Senkrechtparkfeldern
9B Anordnung bei Schrägparkfeldern
W Parkfeldwinkel
Ds Abstände Stütze zur Fahrgasse
As Abstände Stütze zum Parkfeld
Aw / Dw Abstände zur Wand
Zulässiger Bereich für Stützen, Leitungen usw.

Abb. 9
Anordnung von Wänden und Stützen bei Schräg- und Senkrechtparkfeldern

9A Disposition à côté des cases de stationnement perpendiculaires
9B Disposition à côté des cases de stationnement obliques
W Angle de stationnement
Ds Distance entre pilier et allée de circulation
As Distance entre pilier et case de stationnement
Aw / Dw Distance à une paroi
Zone admissible pour les piliers, conduites, etc.

Fig. 9
Disposition des parois et des piliers à côté des cases de stationnement obliques ou perpendiculaires

Anmerkung zur Stützenform
Grundsätzlich sind Stützen mit rundem oder ovalem Querschnitt und glatter Oberfläche zu empfehlen. Diese haben gegenüber rechteckigen Stützen leichte Vorteile in Bezug auf die Platzbeanspruchung. Weiter besteht bei runden oder ovalen Stützen wegen ihrer kantenlosen Form ein geringeres Risiko für Karosserieschäden an Fahrzeugen (z.B. beim Öffnen der Autotüre).

Remarque concernant la forme des piliers
En principe, les piliers de forme circulaire ou ovale avec une surface lisse sont recommandées. En ce qui concerne l'espace nécessaire, ces formes présentent de légers avantages par rapport aux piliers de forme rectangulaire. De plus, vu l'absence d'arêtes sur les piliers circulaires ou ovales le risque de dégâts aux carosseries des véhicules est moindre (p.ex. lors de l'ouverture des portières).

© REGnorm

Licensed to: Nicolò Guffanti (vss@tramos.ch) / Downloaded 26.03.2026

Abstände zu Wänden und Stützen bei Schräg- und Senkrechtparkfeldern *Distances entre parois ou piliers et cases de stationnement obliques ou perpendiculaires*					
Parkfeldwinkel *Angle de stationnement*	Abstände zu Stützen *Distance à un pilier*			Abstand zur Wand *Distance à une paroi*	
			Maximal *Au maximum*		
W	$Ds1$ / $As1$ [m]	$Ds1$ / $As2$ [m]	$Ds2$ [m]	Dw [m]	Aw [m]
90°	0,00 / 0,30	0,80 / 0,10	1,10	1,20	0,30
75°	0,00 / 0,30	0,80 / 0,10	1,05	1,15	0,30
70°	0,00 / 0,35	0,75 / 0,10	1,00	1,10	0,35
60°	0,00 / 0,35	0,70 / 0,10	0,95	1,05	0,40
45°	0,00 / 0,25	0,55 / 0,10	0,80	0,85	0,45
30°	0,00 / 0,10	0,40 / 0,10	0,55	0,60	0,60

Bei Zwischenmassen von $Ds1$ für einen bestimmten Parkfeldwinkel können die Werte As linear zwischen $As1$ und $As2$ interpoliert werden.

Tab. 10
Abstände zu Wänden und Stützen bei Schräg- und Senkrechtparkfeldern

En cas de valeurs intermédiaires $Ds1$ pour un angle de stationnement donné, les distances As peuvent être interpolées linéairement entre $As1$ et $As2$.

Tab. 10
Distances entre parois ou piliers et cases de stationnement obliques ou perpendiculaires

17 Vertikale Abmessungen

In Parkierungsanlagen gilt in Abweichung zu VSS 40 201 [4] eine minimale lichte Höhe LH von 2,30 m. Die lichte Höhe wird von der Fahrbahnoberfläche bis zum niedrigsten Element (Signal, Beleuchtung, Tragwerk usw.) gemessen. Die signalisierte Höhenbegrenzung soll 0,05 m bis 0,10 m tiefer sein als die minimale lichte Höhe.
Bei Schräg- und Senkrechtparkfeldern mit Parkfeldwinkeln von 70° bis 90° kann nötigenfalls im Bereich der Fahrzeugfront bis 1,50 m ab Vorderkante des Parkfeldes das Lichtraumprofil zugunsten von technischen Installationen reduziert werden.
Als Anhaltspunkt gelten folgende Empfehlungen: Bis 1,00 m ab Vorderkante des Parkfeldes ist eine Reduktion der Höhe LH auf 1,80 m möglich. Bei 1,50 m ab Vorderkante ist noch eine Reduktion auf 2,10 m möglich.

Bedingung ist, dass die Installationen keine Verletzungsgefahr aufweisen und eindeutig markiert werden (z.B. rotweisse Balken). Ergänzend dazu sollen die effektiven Höhen signalisiert und ein Hinweis angebracht werden, dass vorwärts einparkiert werden muss.

17 Dimensions verticales

En dérogation à la VSS 40 201 [4] une hauteur libre LH minimale de 2,30 m est applicable. La hauteur libre se mesure de la surface de la chaussée à l'élément le plus bas au plafond (signal, éclairage, élément porteur, etc.). La limitation en hauteur indiquée à l'entrée sera inférieure de 0,05 m à 0,10 m par rapport à la hauteur libre minimale.
Devant les cases de stationnement obliques ou perpendiculaires, avec un angle de stationnement entre 70° et 90°, on peut si nécessaire réduire le gabarit d'espace libre dans la zone de l'avant du véhicule jusqu'à 1,50 m depuis le bord avant de la case pour placer des équipements techniques.
De manière indicative, les recommandations suivantes peuvent être faites: jusqu'à 1,00 m depuis l'avant de la case, une réduction de la hauteur LH à 1,80 m est possible; à 1,50 m de l'avant de la case, une réduction à 2,10 m est possible.
Dans ce cas, les conditions sont les suivantes: les équipements ne doivent présenter aucun danger de blessure et être marqués de façon claire (p.ex. bandes rouge et blanche). De plus, les hauteurs effectives, ainsi que l'indication d'entrer dans la case en marche avant doivent être signalées.

18 Quergefälle

Das maximale Quergefälle von Parkfeldern beträgt 6%, bei rollstuhlgerechten Parkfeldern 2%.

18 Dévers

La pente transversale maximale des cases de stationnement est de 6%, celle des cases de stationnement adaptées aux fauteuils roulants est de 2%.

19 Entwässerung der Verkehrsflächen

Parkierungsanlagen müssen eine auf die Entwässerung ausgerichtete Oberfläche mit Gefälle haben. Für gedeckte und ungedeckte Verkehrsflächen in Parkierungsanlagen gelten die Empfehlungen der VSS 40 292 [11].

19 Evacuation des eaux des surfaces de circulation

La surface des installations de stationnement doit être inclinée afin de permettre l'évacuation des eaux. Concernant les surfaces de circulation couvertes et non couvertes des installations de stationnement, les recommandations de la VSS 40 292 [11] s'appliquent.

© REGnorm

Licensed to: Nicolò Guffanti (vss@tramos.ch) / Downloaded 26.03.2026

F Geometrie der Zu- und Wegfahrtsanlagen

20 Fahrwege

20.1 Lichtraumprofil

Das Normalprofil der Fahrwege ist in Abbildung 10 dargestellt. Die lichte Breite ist die Summe aus der Fahrbahnbreite und den Breiten der beidseitigen Schrammborde. Die lichten Breiten und die Fahrbahnbreiten sind in den Tabellen 12 und 13 enthalten.
Installationen wie Leitungen, Dämmungen, Garagentore mit Führungselementen usw. müssen ausserhalb des Lichtraumprofils platziert werden.

F Géométrie des installations d'accès et de sortie

20 Voies de liaison

20.1 Gabarit d'espace libre

Le profil type des voies de liaison est représenté à la figure 10. La largeur libre résulte de la somme de la largeur de la chaussée et des largeurs des deux bordures de protection. Les largeurs libres et les largeurs de chaussée figurent aux tableaux 12 et 13.
Les équipements tels que conduites, isolations, portes de garage avec éléments de commande, etc. seront placés en dehors du gabarit d'espace libre.

© REGnorm

Licensed to: Nicolò Guffanti (vss@tramos.ch) / Downloaded 26.03.2026

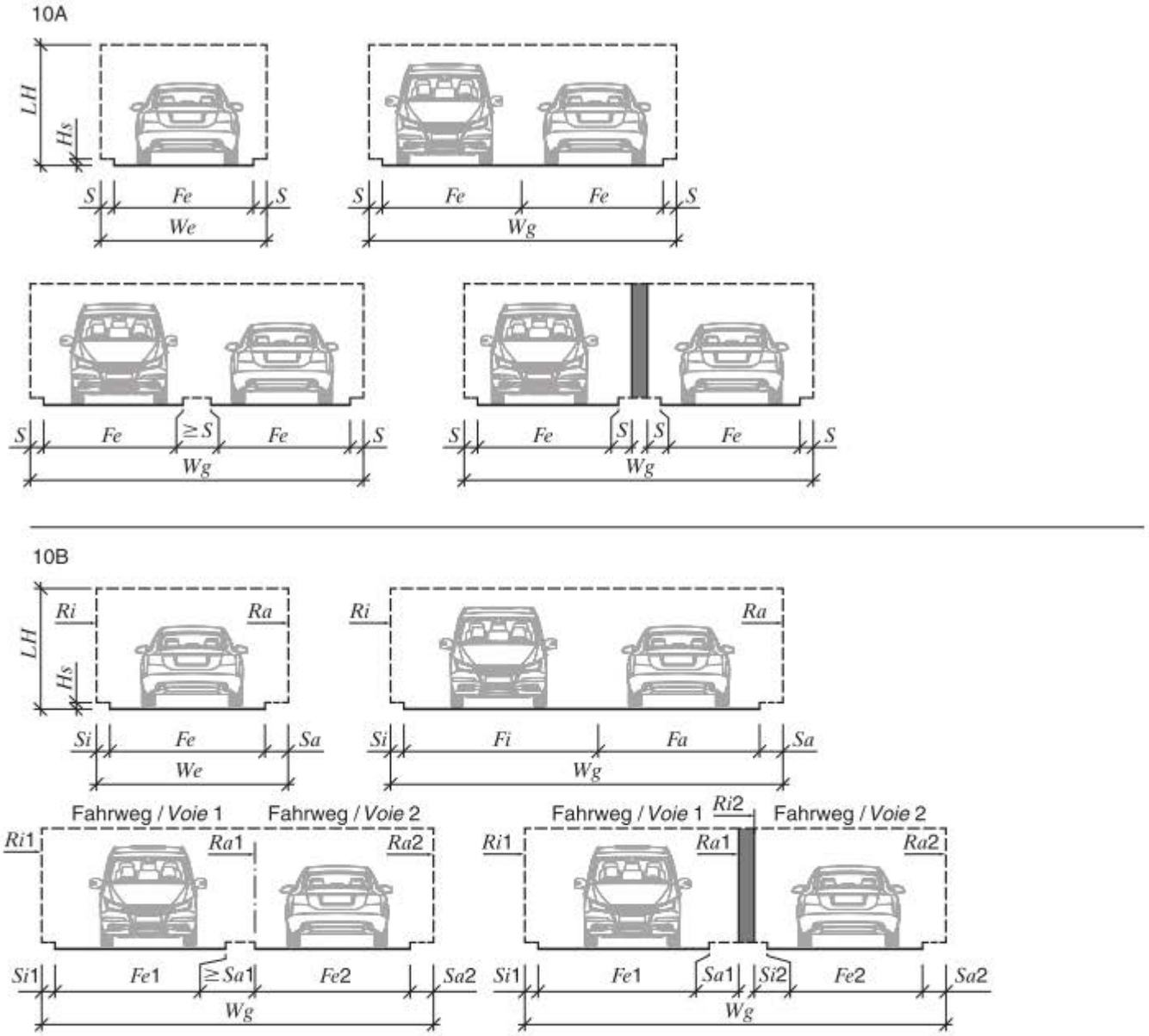

10A Fahrwege in Geraden
10B Fahrwege in Kurven

Fe Breite der Fahrbahn (in Geraden oder in Abhängigkeit der Kurvenradien)
Fa Breite des äusseren Fahrstreifens
Fi Breite des inneren Fahrstreifens
S Breite des Schrammbords
Sa Breite des äusseren Schrammbords
Si Breite des inneren Schrammbords
Hs Höhe des Schrammbords
Ra Aussenradius des Fahrweges
Ri Innenradius des Fahrweges
We Lichte Breite des Fahrweges mit Einbahnverkehr
Wg Lichte Breite des Fahrweges mit Gegenverkehr

LH Lichte Höhe

Abb. 10
Normalprofil von Fahrwegen im Einbahn- und Gegenverkehr

10A Voies de liaison en alignement
10B Voies de liaison en courbe

Fe Largeur de la chaussée (en alignement ou en fonction du rayon de courbure)
Fa Largeur de la voie de circulation extérieure
Fi Largeur de la voie de circulation intérieure
S Largeur de la bordure de protection
Sa Largeur de la bordure de protection extérieure
Si Largeur de la bordure de protection intérieure
Hs Hauteur de la bordure de protection
Ra Rayon extérieur de la voie de liaison
Ri Rayon intérieur de la voie de liaison
We Largeur libre de la voie de liaison à sens unique
Wg Largeur libre de la voie de liaison à trafic bidirectionnel
LH Hauteur libre

Fig. 10
Profil type des voies de liaison à sens unique et à trafic bidirectionnel

© REGnorm

Licensed to: Nicolò Guffanti (vss@tramos.ch) / Downloaded 26.03.2026

Bei Fahrwegen mit Gegenverkehr und baulicher Trennung zwischen den beiden Fahrtrichtungen sind für jede Richtung die Werte von Fahrwegen mit Einbahnverkehr gemäss Tabelle 11 anzuwenden. Erfolgt die bauliche Trennung mit einem Schrammbord, muss dieses mindestens die erforderliche Breite für die innere Fahrbahn aufweisen. Erfolgt die bauliche Trennung mit einer Wand oder Stützen, sind auf beiden Seiten die entsprechenden Schrammbordwerte für jede Richtung separat zu berücksichtigen.

20.2 Lichte Höhe

In Übereinstimmung mit den vertikalen Abmessungen in Parkierungsanlagen gemäss Ziffer 17 gilt auch für die Fahrwege eine minimale lichte Höhe LH von 2,30 m. Die lichte Höhe wird von der Fahrbahnoberfläche bis zum niedrigsten Element (Schrankensysteme, Beleuchtung usw.) gemessen. Im Bereich von Wannen und Kuppen ist ein entsprechender Höhenzuschlag (in der Regel 0,05 m) zu berücksichtigen. Die signalisierte Höhenbegrenzung soll 0,05 m bis 0,10 m tiefer sein als die minimale lichte Höhe.

20.3 Schrammborde

Die Schrammborde sind Bestandteil der lichten Breite und werden in der Regel baulich ausgebildet. Sie sind 0,10 m bis 0,12 m hoch und die Kanten sind anzufasen (etwa 20 mm • 20 mm). In Geraden und beim Innenrand von Kurven haben die Schrammborde eine Breite von 0,25 m. Beim Aussenrand von Kurven ist die Breite vom Radius abhängig und in den Tabellen 11 und 12 angegeben.

20.4 Kurvenverbreiterungen

Die Fahrwegbreiten in Kurven sind vom Radius abhängig. Sie sind für Einbahnverkehr in Abbildung 11 und Tabelle 11, für Gegenverkehr in Abbildung 12 und Tabelle 12 dargestellt.

Sur les voies de liaison à trafic bidirectionnel avec séparation physique des deux sens de circulation, on utilisera pour chaque sens de circulation les valeurs des voies de liaison à sens unique selon le tableau 11. Si la séparation est constituée d'une bordure de protection, celle-ci doit au moins avoir la largeur nécessaire pour la chaussée intérieure. Si la séparation physique est constituée d'une paroi ou de piliers, on utilisera de chaque côté, pour les bordures de protection, les valeurs correspondantes séparément pour chaque sens.

20.2 Hauteur libre

En conformité avec les dimensions verticales dans les installations de stationnement selon le chiffre 17, une hauteur libre LH minimale de 2,30 m vaut également pour les voies de liaison. La hauteur libre est mesurée entre la surface de la chaussée et l'élément le plus bas (systèmes de barrières, éclairage, etc.). Dans les zones de raccordements concaves et convexes on augmentera la hauteur (en général de 0,05 m). La limitation de hauteur signalée doit être inférieure de 0,05 m à 0,10 m à la hauteur libre minimale.

20.3 Bordures de protection

Les bordures de protection qui sont en principe à aménager font partie de la largeur libre. Elles doivent donc être conçues en conséquence. Elles auront une hauteur de 0,10 m à 0,12 m et leurs arêtes seront chanfreinées (environ 20 mm • 20 mm). En alignement et sur le bord intérieur des courbes, les bordures de protection auront une largeur de 0,25 m. Sur le bord extérieur des courbes, la largeur dépend du rayon. Celle-ci figure aux tableaux 11 et 12.

20.4 Surlargeurs en courbe

Les largeurs des voies de liaison en courbe dépendent de leur rayon. La figure 11 et le tableau 11 fournissent les indications pour la circulation à sens unique, la figure 12 et le tableau 12 pour la circulation bidirectionnelle.

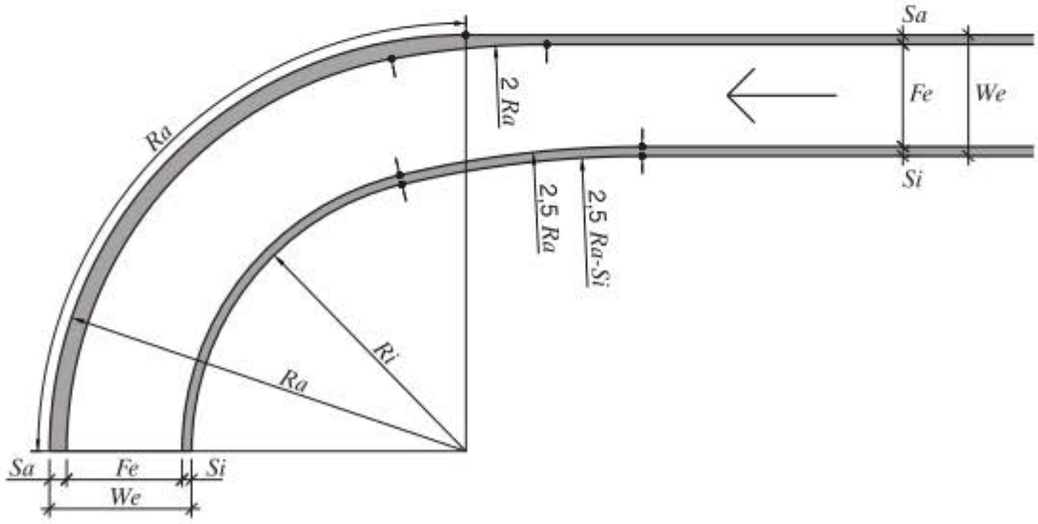

- • Tangentenpunkt
- *Fe* Breite der Fahrbahn (in Geraden oder in Abhängigkeit der Kurvenradien)
- *Sa* Breite des äusseren Schrammbords
- *Si* Breite des inneren Schrammbords
- *Ra* Aussenradius des Fahrweges
- *Ri* Innenradius des Fahrweges
- *We* Lichte Breite des Fahrweges

Abb. 11
Definition der geometrischen Elemente für Fahrwege mit Einbahnverkehr

- • Point de tangence
- *Fe* Largeur de la chaussée (en alignement ou en fonction du rayon de courbure)
- *Sa* Largeur de la bordure de protection extérieure
- *Si* Largeur de la bordure de protection intérieure
- *Ra* Rayon extérieur de la voie de liaison
- *Ri* Rayon intérieur de la voie de liaison
- *We* Largeur libre de la voie de liaison

Fig. 11
Définition des éléments géométriques pour les voies de liaison avec circulation à sens unique

© REGnorm

Licensed to: Nicolò Guffanti (vss@tramos.ch) / Downloaded 26.03.2026

Abmessungen der Fahrwege mit Einbahnverkehr ***Dimensions des voies de liaison à sens unique***					
Aussenradius des Fahrweges *Rayon extérieur de la voie de liaison* *Ra* [m]	Breite des äusseren Schrammbordes *Largeur de la bordure extérieure de protection* *Sa* [m]	Breite der Fahrbahn *Largeur de la chaussée* *Fe* [m]	Breite des inneren Schrammbordes *Largeur de la bordure intérieure de protection* *Si* [m]	Innenradius des Fahrweges *Rayon intérieur de la voie de liaison* *Ri* [m]	Lichte Breite des Fahrweges *Largeur libre de la voie de liaison* *We* [m]
7,50	0,65	3,40	0,25	3,20	4,30
8,00 8,50	0,60 0,55	3,35 3,30	0,25 0,25	3,80 4,40	4,20 4,10
9,00 9,50	0,55 0,50	3,25 3,20	0,25 0,25	4,95 5,55	4,05 3,95
10,00 10,50	0,50 0,50	3,15 3,10	0,25 0,25	6,10 6,65	3,90 3,85
11,00 11,50	0,45 0,45	3,05 3,05	0,25 0,25	7,25 7,75	3,75 3,75
12,00 13,00 14,00 15,00	0,45 0,40 0,40 0,35	3,00 2,95 2,95 2,90	0,25 0,25 0,25 0,25	8,30 9,40 10,40 11,50	3,70 3,60 3,60 3,50
20,00 25,00…∞	0,30 0,25	2,70 2,70	0,25 0,25	16,75 21,80…∞	3,25 3,20

Tab. 11
Abmessungen der Fahrwege mit Einbahnverkehr

Tab. 11
Dimensions des voies de liaison à sens unique

Bei engen Platzverhältnissen und geringem Verkehrsaufkommen sind Minderbreiten von maximal 0,20 m für die Fahrbahn und je 0,05 m für die Schrammborde möglich, bewirken aber eine Komforteinbusse und erfordern entsprechend tiefe Geschwindigkeiten.

Si l'espace à disposition est restreint et que le trafic est faible, il est possible de diminuer la largeur de la chaussée de 0,20 m au maximum et celle de chaque bordure de protection de 0,05 m au maximum. Ceci occasionne toutefois une diminution du confort et nécessite de circuler à vitesse réduite.

© REGnorm

Licensed to: Nicolò Guffanti (vss@tramos.ch) / Downloaded 26.03.2026

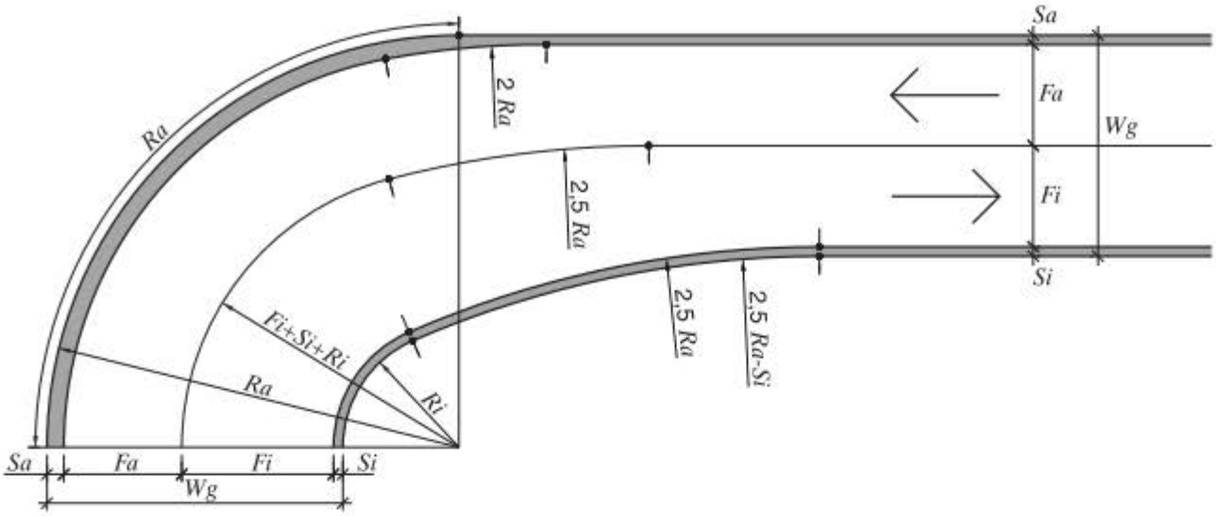

- • Tangentenpunkt
- *Fa* Breite des äusseren Fahrstreifens
- *Fi* Breite des inneren Fahrstreifens
- *Sa* Breite des äusseren Schrammbords
- *Si* Breite des inneren Schrammbords
- *Ra* Aussenradius des Fahrweges
- *Ri* Innenradius des Fahrweges
- *Wg* Lichte Breite des Fahrweges

Abb. 12
Definition der geometrischen Elemente für Fahrwege mit Gegenverkehr

- • Point de tangence
- *Fa* Largeur de la voie de circulation extérieure
- *Fi* Largeur de la voie de circulation intérieure
- *Sa* Largeur de la bordure de protection extérieure
- *Si* Largeur de la bordure de protection intérieure
- *Ra* Rayon extérieur de la voie de liaison
- *Ri* Rayon intérieur de la voie de liaison
- *Wg* Largeur libre de la voie de liaison

Fig. 12
Définition des éléments géométriques pour les voies de liaison avec circulation bidirectionnelle

Abmessungen der Fahrwege mit Gegenverkehr ***Dimensions des voies de liaison à trafic bidirectionnel***						
Aussenradius des Fahrweges *Rayon extérieur de la voie de liaison* *Ra* [m]	Breite des äusseren Schramm-bordes *Largeur de la bordure extérieure de protection* *Sa* [m]	Breite des äusseren Fahrstreifens *Largeur de la voie de circulation extérieure* *Fa* [m]	Breite des inneren Fahrstreifens *Largeur de la voie de circulation intérieure* *Fi* [m]	Breite des inneren Schramm-bordes *Largeur de la bordure intérieure de protection* *Si* [m]	Innenradius des Fahrweges *Rayon intérieur de la voie de liaison* *Ri* [m]	Lichte Breite des Fahrweges *Largeur libre de la voie de liaison* *Wg* [m]
11,00 11,50	0,45 0,45	3,15 3,15	4,05 3,95	0,25 0,25	3,10 3,70	7,90 7,80
12,00 13,00 14,00 15,00	0,45 0,40 0,40 0,35	3,10 3,05 3,05 3,00	3,75 3,70 3,55 3,45	0,25 0,25 0,25 0,25	4,45 5,60 6,75 7,95	7,55 7,40 7,25 7,05
20,00 25,00…∞	0,30 0,25	2,80 2,70	3,15 2,70	0,25 0,25	13,50 19,10…∞	6,50 5,90

Tab. 12
Abmessungen der Fahrwege mit Gegenverkehr

Tab. 12
Dimensions des voies de liaison à trafic bidirectionnel

Bei engen Platzverhältnissen und geringem Verkehrsaufkommen sind Minderbreiten von maximal 0,20 m je Fahrstreifen und je 0,05 m für die Schrammborde möglich, bewirken aber eine Komforteinbusse und erfordern entsprechend tiefe Geschwindigkeiten beim Kreuzen.

Si l'espace à disposition est restreint et que le trafic est faible, il est possible de diminuer la largeur de chaque voie de circulation de 0,20 m au maximum et celle de chaque bordure de protection de 0,05 m au maximum. Ceci occasionne toutefois une diminution du confort et nécessite de circuler à vitesse réduite lors des croisements.

© REGnorm

Licensed to: Nicolò Guffanti (vss@tramos.ch) / Downloaded 26.03.2026

20.5 Längsneigung

Die maximale Längsneigung beträgt für ungedeckte Rampen 15% und für gedeckte (oder allenfalls beheizte) Rampen 18%. Die maximale Neigung bezieht sich auf den steileren Fahrbahnrand (z.B. Kurveninnenseite) und gilt auch für das Fallliniengefälle (siehe Abbildung 13).

Wenn Rampen kombiniert von Personenwagen und Velos benutzt werden, sind zudem die Anforderungen der VSS 40 238 «Fussgänger- und leichter Zweiradverkehr; Rampen, Treppen und Treppenwege» [7] und der VSS 40 201 [4] einzuhalten.
Die Entwässerung der Rampen ist so zu konzipieren, dass möglichst wenig Wasser über die Fahrbahn der Rampen fliesst.

20.5 Déclivité

La déclivité maximale des rampes non couvertes sera de 15%. Celle des rampes couvertes (ou évent. chauffées) sera de 18%. La déclivité maximale se rapporte au bord de chaussée le plus raide (p.ex. bord intérieur de la courbe). Cette déclivité vaut aussi pour la ligne de plus grande pente (voir figure 13).
Pour les rampes combinant la circulation des voitures de tourisme et celle des vélos sont appliquées les exigences de la VSS 40 238 «Trafic des piétons et des deux-roues légers; rampes, escaliers et rampes à gradins» [7] et de la VSS 40 201 [4].
L'évacuation des eaux des rampes sera conçue de manière que le moins possible d'eau s'écoule sur la chaussée.

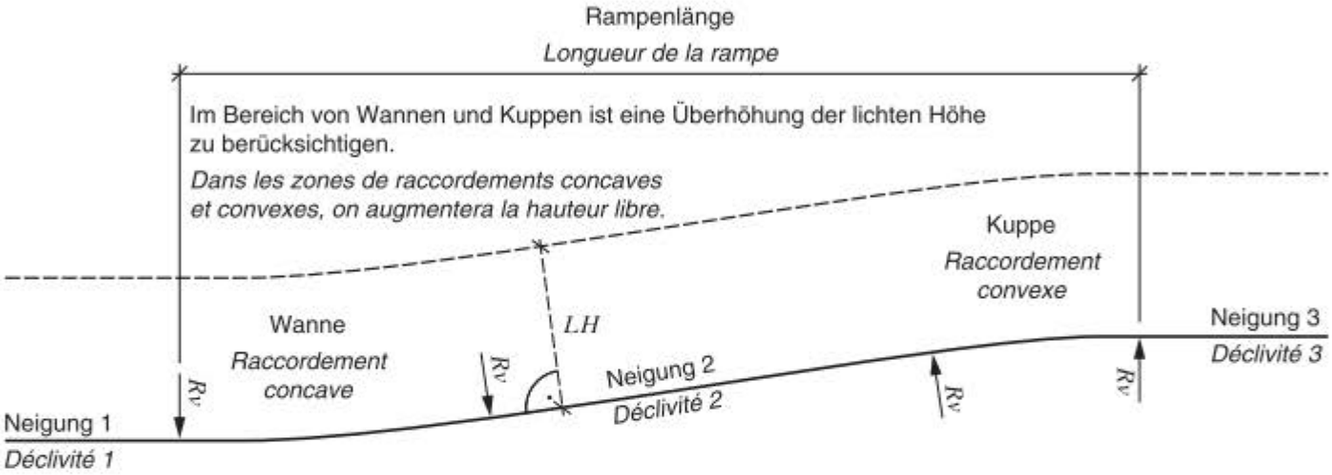

Rv Radius der vertikalen Ausrundung [m]
LH Lichte Höhe

Abb. 13
Elemente der vertikalen Linienführung

Rv Rayon de raccordement vertical [m]
LH Hauteur libre

Fig. 13
Eléments du profil en long

20.6 Änderung der Längsneigung

Änderungen der Längsneigung sind mittels Ausrundungen oder mehreren Neigungsknicken auszuführen. Gefällswechsel ohne Ausrundungen dürfen maximal 6% betragen.

Die minimalen Ausrundungsradien und Abstände der Neigungsknicke sind in Tabelle 13 definiert.

20.6 Changement de déclivité

Les modifications de la déclivité seront réalisées au moyen de raccordements verticaux ou de plusieurs cassures. Les changements de déclivité sans raccordement ne doivent pas excéder 6%.
Les rayons de raccordement minimaux et les distances minimales entre les cassures sont définis au tableau 13.

Minimale Ausrundungsradien und Abstände der Neigungsknicke ***Minima pour les rayons de raccordement et les distances entre les cassures***		
Element der Parkierungsanlage *Elément de l'installation de stationnement*	Ausrundungsradius *Rayon de raccordement* *Rv* [m]	Abstand der Neigungsknicke *Distance entre les cassures* [m]
Kuppe *Raccordement convexe*	20	2,00
Wanne *Raccordement concave*	30	3,00

Tab. 13
Minimale Ausrundungsradien und Abstände der Neigungsknicke

Tab. 13
Minima pour les rayons de raccordement et les distances entre les cassures

© REGnorm

Licensed to: Nicolò Guffanti (vss@tramos.ch) / Downloaded 26.03.2026

21 Ein- und Ausfahrt mit Kontrolleinrichtungen

Die Anordnung von Kontrolleinrichtungen ist in Abbildung 14 dargestellt.

21 Entrée et sortie avec dispositifs de contrôle

La disposition des dispositifs de contrôle est représentée à la figure 14.

14A

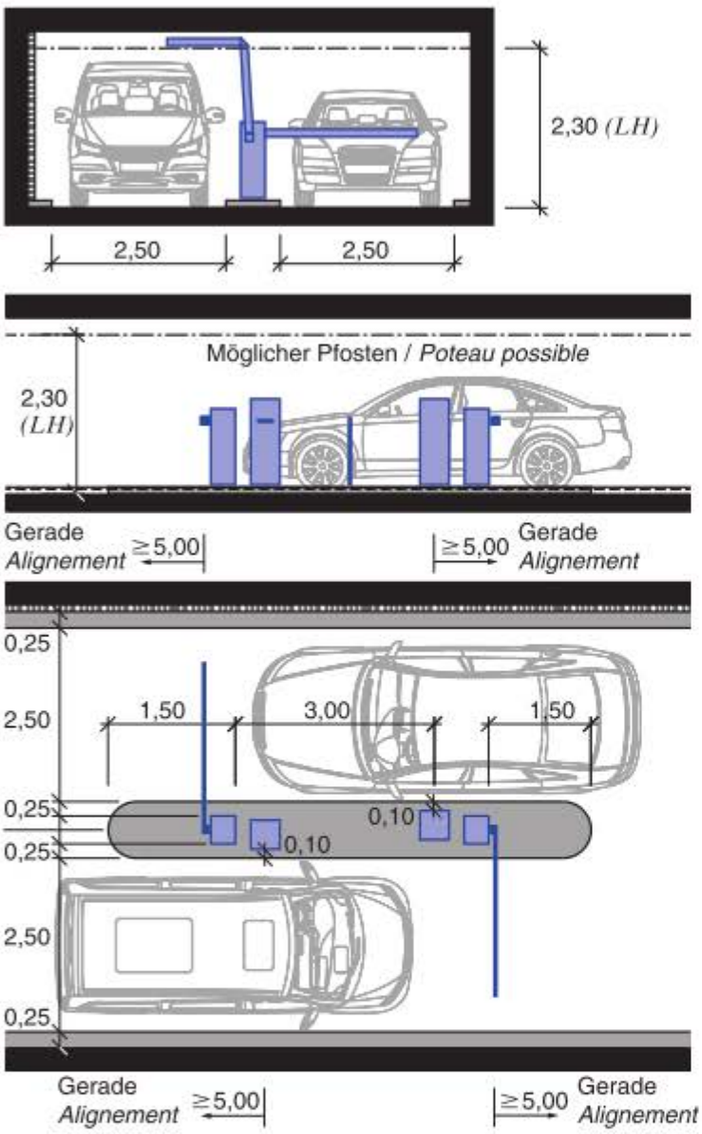

14B

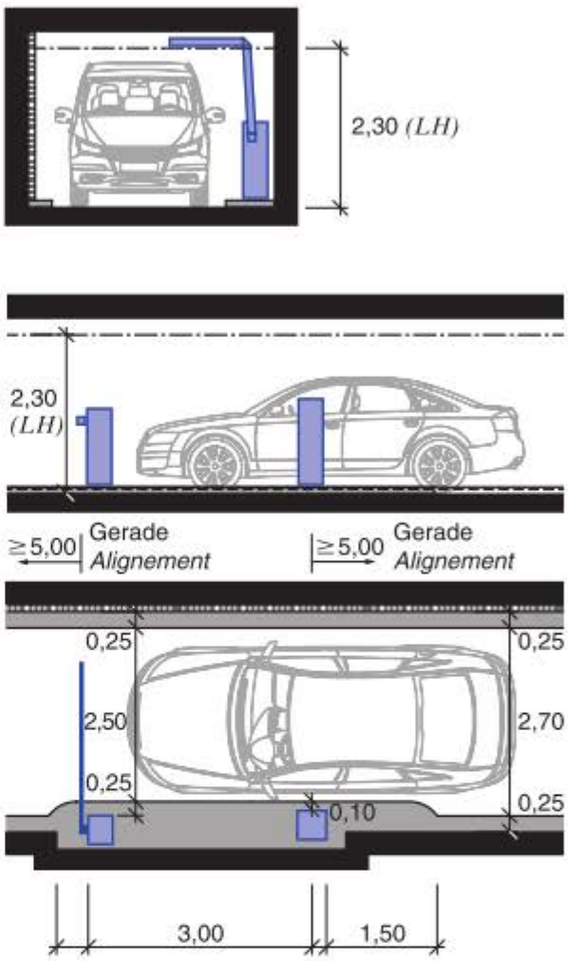

14A Zu- und Wegfahrt kombiniert mit Kontrolleinrichtung
14B Zu- und Wegfahrt einzeln mit Kontrolleinrichtung

LH Lichte Höhe

Abb. 14
Anordnung und Abmessungen [m] von Kontrolleinrichtungen mit Ticketautomat

14A Entrée et sortie combinées avec dispositif de contrôle
14B Entrée et sortie séparées avec dispositif de contrôle

LH Hauteur libre

Fig. 14
Disposition et dimensions [m] de dispositifs de contrôle avec automate distributeur de tickets

Die Kontrolleinrichtungen sollen in Geraden liegen. Vor dem ersten Automaten und nach der Schranke ist eine gerade Fahrstrecke von mindestens 5,00 m erforderlich. Die Längsneigung des Fahrweges im Bereich der Kontrolleinrichtungen darf maximal 3% betragen.
Bei Kontrolleinrichtungen von Anlagen mit Veloabstellplätzen sind die Anforderungen des Veloverkehrs zu berücksichtigen.

Les dispositifs de contrôle seront placés dans les alignements. Un tronçon rectiligne d'au moins 5,00 m est nécessaire avant le premier automate et après la barrière. La déclivité de la voie de liaison au niveau des dispositifs de contrôle sera au maximum de 3%.
Dans le cas des installations avec stationnement de vélos, les dispositifs de contrôle intégreront les exigences du trafic cycliste.

© REGnorm

Licensed to: Nicolò Guffanti (vss@tramos.ch) / Downloaded 26.03.2026

22 Ein- und Ausfahrt mit Toranlagen

Die Anordnung von Toranlagen ist in Abbildung 15 dargestellt.

22 Entrée et sortie avec portes

La disposition de portes est représentée à la figure 15.

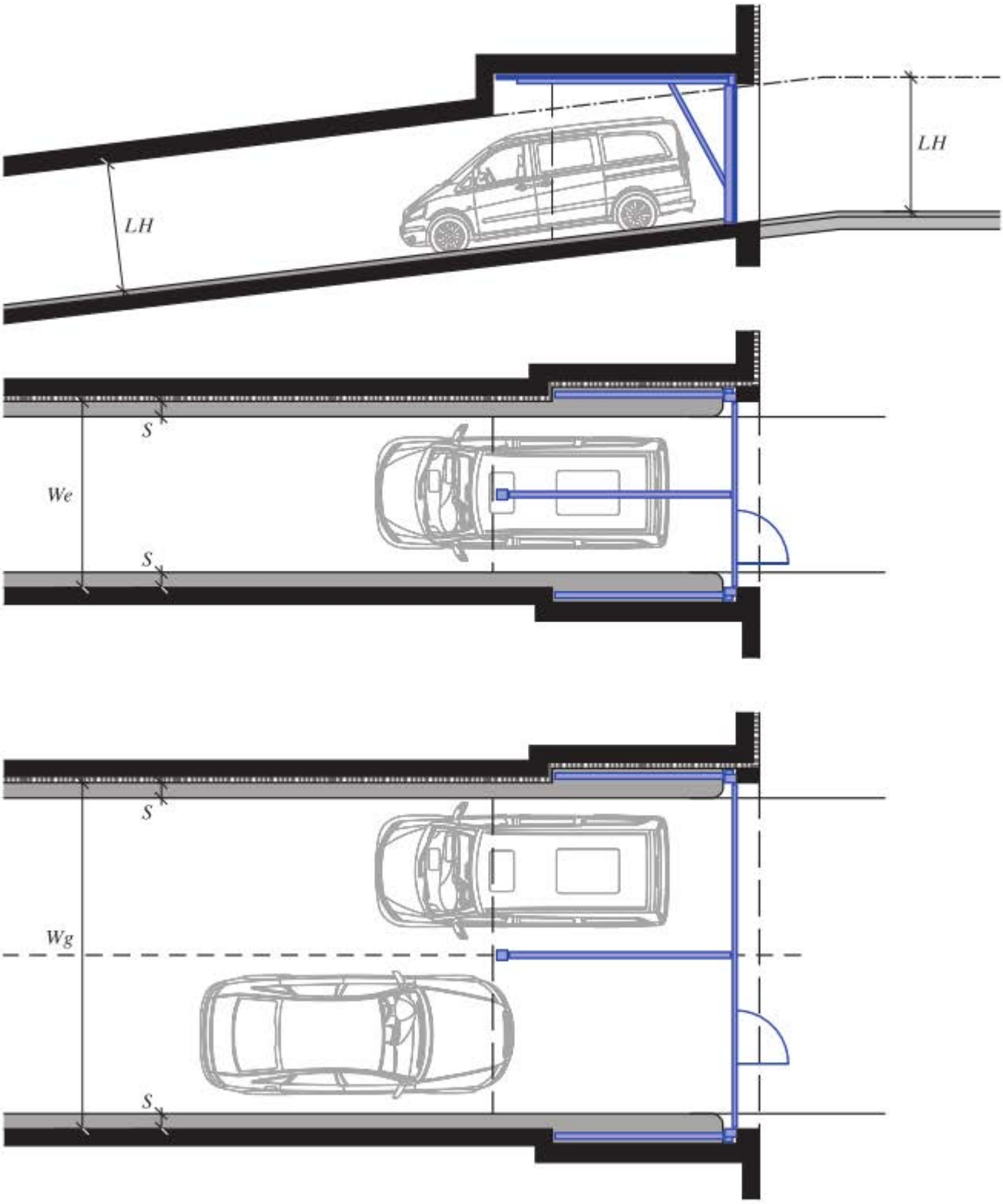

LH Lichte Höhe
We Lichte Breite des Fahrweges mit Einbahnverkehr
Wg Lichte Breite des Fahrweges mit Gegenverkehr

S Breite des Schrammbords

Abb. 15
Anordnungen von Toranlagen

LH Hauteur libre
We Largeur libre de la voie de liaison à sens unique
Wg Largeur libre de la voie de liaison à trafic bidirectionnel
S Largeur de la bordure de protection

Fig. 15
Disposition de portes

© REGnorm

Licensed to: Nicolò Guffanti (vss@tramos.ch) / Downloaded 26.03.2026

G Literaturverzeichnis

[1] VSS 40 050 Grundstückzufahrten; Anordnung und Gestaltung
[2] VSS 40 066 Parkieren; Projektierung von Veloparkierungsanlagen
[3] VSS 40 075 Fussgängerverkehr; Hindernisfreier Verkehrsraum (inklusive normativer Anhang)
[4] VSS 40 201 Geometrisches Normalprofil; Grundabmessungen und Lichtraumprofil der Verkehrsteilnehmer
[5] VSS 40 211 Entwurf des Strassenraumes; Grundlagen
[6] VSS 40 213 Entwurf des Strassenraumes; Verkehrsberuhigungselemente
[7] VSS 40 238 Fussgänger- und leichter Zweiradverkehr; Rampen, Treppen und Treppenwege
[8] VSS 40 273 Knoten; Sichtverhältnisse in Knoten in einer Ebene
[9] VSS 40 280 Parkieren; Grundlagen
[10] VSS 40 281 Parkieren; Angebot an Parkfeldern für Personenwagen
[11] VSS 40 292 Parkieren; Gestaltung und Ausrüstung der Parkierungsanlagen
[12] VSS 40 303 Strassenprojektierung; Entwurf von Hauptverkehrsstrassen innerorts
[13] SIA 500 / SN 521 500 Hindernisfreie Bauten
[14] Bundesamt für Strassen ASTRA; Geometrie des Fahrzeugparks der Schweiz, Forschungsbericht Nr. 1569, Bern, 2016

G Bibliographie

[1] VSS 40 050 Accès riverains; disposition et aménagement
[2] VSS 40 066 Stationnement; conception des aménagements de stationnement pour vélos
[3] VSS 40 075 Trafic piétonnier; espace de circulation sans obstacles (y compris annexe normative)
[4] VSS 40 201 Profil géométrique type; dimensions de base et gabarit des usagers de la route
[5] VSS 40 211 Conception de l'espace routier; bases
[6] VSS 40 213 Conception de l'espace routier; éléments de modération du trafic
[7] VSS 40 238 Trafic des piétons et des deux-roues légers; rampes, escaliers et rampes à gradins
[8] VSS 40 273 Carrefours; conditions de visibilité dans les carrefours à niveau
[9] VSS 40 280 Stationnement; bases
[10] VSS 40 281 Stationnement; offre en cases de stationnement pour les voitures de tourisme
[11] VSS 40 292 Stationnement; conception et équipement des installations de stationnement
[12] VSS 40 303 Projets routiers; conception de routes principales à l'intérieur des localités
[13] SIA 500 / SN 521 500 Constructions sans obstacles
[14] Office fédéral des routes OFROU; Caractéristiques géométriques du parc de véhicules circulant en Suisse, rapport de recherche nº 1569, Berne, 2016

© REGnorm